Áreas Protegidas de la Cuenca Rio Yaque del Norte (CRYN) y Cuenca del Rio Yuna (CRY)

Fichas resúmenes

I. Áreas Protegidas en la Cuenca del Rio Yaque del Norte (CRYN).

En la cuenca del Yaque del Norte existe un 34.09% del territorio bajo el Sistema Nacional de Áreas Protegidas (6 categorías) [1,2], con total de 23 sitios con algún tipo de protección, que incluyen:

1. **Áreas de Protección Estricta**: Ébano Verde, Dicayagua y Villa Elisa
2. **Parques Nacionales***: Armando Bermúdez, Baiguate, José del Carmen Ramírez, Manglares de Estero Balsa, Nalga de Maco y Picky Lora.
3. **Monumentos Naturales**: Diego de Ocampo, La Tinaja y el Salto de Jimenoa.
4. **Áreas de Manejo de Hábitat**: Río Chacuey y el Cañón del Río Gurabo.
5. **Las Reservas Naturales**: Alto Bao, Alto Mao, Cerro Chacuey, Las Matas y Río Cana.
6. **Paisajes Protegidos**: Vía Panorámica Carretera Bayacanes-Jarabacoa, Carretera El Abanico–Constanza, Carretera Santiago-La Cumbre-Puerto Plata y la Entrada de Mao.

El manejo de las áreas protegidas de la República Dominicana, se hace al amparo de las Ley 202-04, que tiene como objetivo:..."garantizar la conservación de muestras representativas de los diferentes ecosistemas y del patrimonio natural y cultural de la República Dominicana para asegurar la permanencia y optimización de los servicios ambientales y económicos que estos ecosistemas ofrecen o puedan ofrecer a la sociedad dominicana en la presente y futuras generaciones"… (Art. 1. Ley 202-04) y de la Ley 64-00.

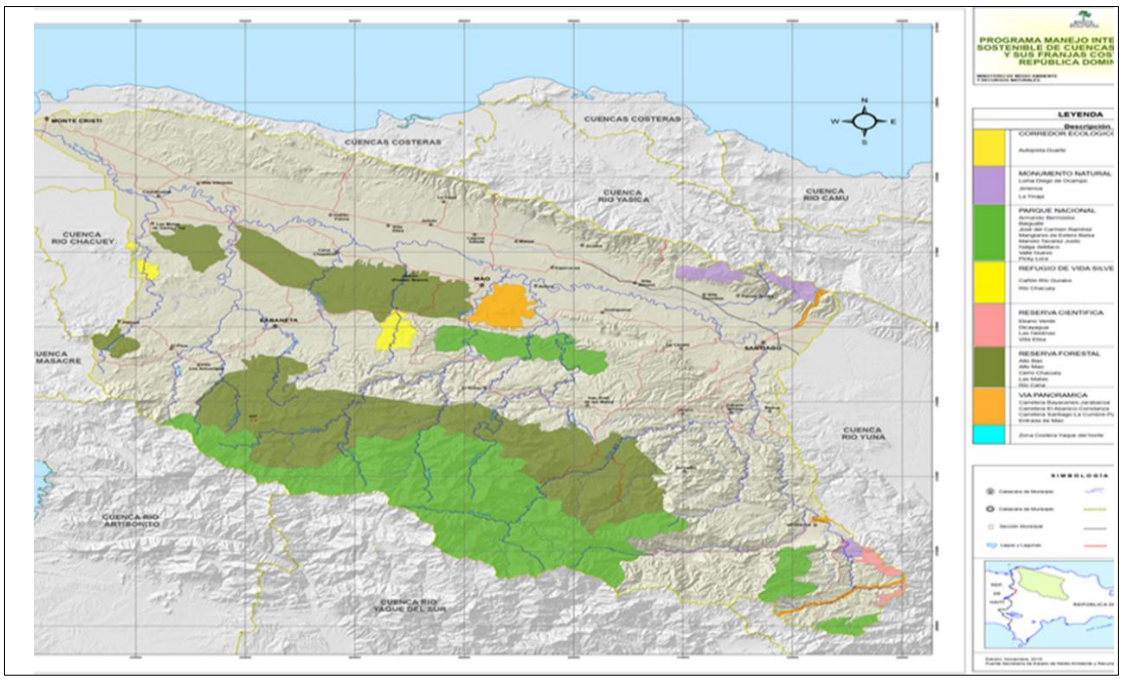

Figura 1. Cuenca Yaque del Norte. Áreas Protegidas en la CRYN[2]

A continuación incluimos unas fichas resúmenes de las características principales de las áreas protegidas presentes en la Cuenca Yaque del Norte, elaboradas a partir de informaciones disponibles en internet y en documentos suministrados por el Viceministerio de Áreas Protegidas y Biodiversidad, que han sido las fuentes principales consultadas. Ha sido notorio la disparidad de informaciones, pues mientras en algunas áreas protegidas aparecen diversos trabajos realizados, en otras, las informaciones son realmente escasas.

Simbología general:

- UICN (2012): VU= Vulnerable; CR= Peligro Crítico; EN= En Peligro
- MA= Ministerio Ambiente (2011): VU= Vulnerable; PC= Peligro Crítico; EP= En Peligro
- Estatus: I= Introducidas E= Endémicas N= Nativas
- DB= Distribución Biogeográfica: rd-am= República Dominicana/Amplia; rd-r= República Dominicana/ restringida; t-r= Toda Isla/restringida; rd-r= República Dominicana/ restringida

[1] https://ambiente.gob.do/cuencas-hidrograficas/yaque-del-norte/

[2] http://ambiente.gob.do/wp-content/uploads/2016/11/Yaque-del-Norte-Areas-Protegidas-1.pdf

*Nota: el Parque Nacional Valle Nuevo aparece en los mapas de áreas protegidas de la Cuenca del Rio Yaque del Norte (CRYN) y de la Cuenca del Rio Yuna (CRY). Lo hemos incluido en la descripción de la Cuenca del Yuna

RESERVA CIENTÍFICA ÉBANO VERDE

Creación: 28 de octubre de 1989. Decreto No.417-89

Administración: Fundación para el Mejoramiento Humano (PROGRESSIO)

Categoría: Área de Protección Estricta

Ubicación: La Reserva Científica Ébano Verde (RCEV) está localizada en la Cordillera Central, es contigua a la Reserva Científica Las Neblinas y al norte del Parque Nacional Valle Nuevo. Cruza a sus orillas la carretera que va hacia el Municipio de Constanza y sus comunidades. Tiene 29 kilómetros cuadrados, originalmente fue creada con 23.1 kilómetros cuadrados. Se encuentra ubicada en la parte oriental de la Cordillera Central, entre los municipios de Jarabacoa, Constanza, Bonao y La Vega. (Viceministerio de Áreas Protegidas y Biodiversidad. 2017).

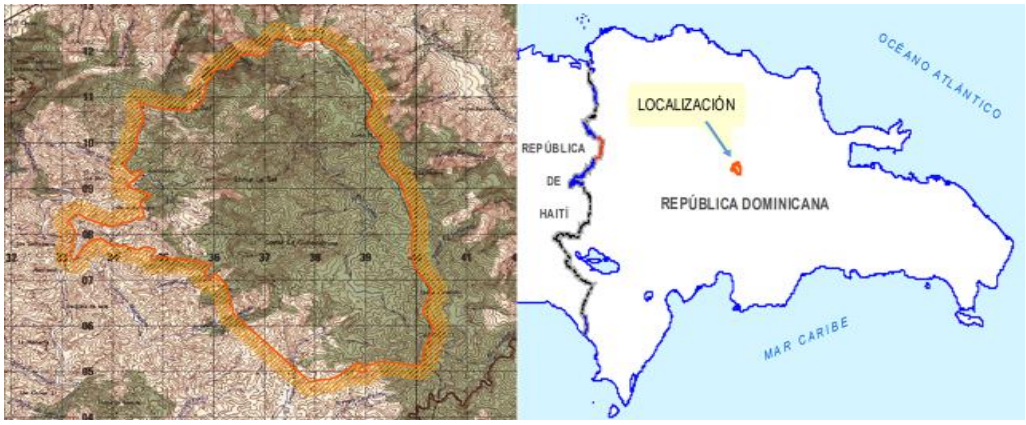

Figura 2. Ubicación de la Reserva Científica Ébano Verde[3]

Topografía, hidrología, clima y paisajes.

Esta área está clasificada como "Bosque muy húmedo Montano Bajo", según Holdridge. Toda la reserva está conformada por una topografía abrupta, con una pendiente sobre el 30% de inclinación. Su elevación varía de 800 a 1,565 (Loma La Golondrina). La pluviometría oscila entre 1,500 y 3,000 mm anuales. En general, su vegetación está compuesta por áreas de Bosque Nublado, Bosque de Manaclas y Bosque de Ribera, así como fragmentos de Bosque Secundario en diferentes estadios de crecimiento. El Bosque Nublado es del tipo latifoliado, donde domina el árbol que da su nombrea esta reserva, el Ebano verde (*Magnolia pallescens*). El Manaclar está dominado por la Palma Manacla (*Prestoea montana*), mientras que en el Bosque de Ribera las especies más comunes son el Auquey (*Myrcia splendens*), la Cigua prieta (*Ocotea leucoxylon*), Roble (*Tabebuia bullata*) y Cafetán (*Psychotria berteriana*).[4]

Flora.

La flora de esta área natural protegida está compuesta de 621 especies de plantas vasculares, de las cuales 153 son endémicas de la Hispaniola, lo que le da a su flora un alto endemismo. La especie endémica más característica del área es el Ébano verde (*Magnolia pallescens*), un árbol de madera preciosa en vías de extinción. (Viceministerio de Áreas Protegidas y Biodiversidad, 2017). Entre los representantes de la flora, se destacan las orquídeas, con el mayor número de especies (81) por familia. De nuevo la familia Orquidaceae se destaca como el grupo con el mayor número de especies endémicas (por lo menos 21 especies). Entre las especies más interesantes, se encuentra la planta carnívora Pinguicola casabitoana, sólo conocida para el área de la RCEV, específicamente en su sendero denominado Baño de Nubes. Otras especies de plantas importantes para la conservación son *Antirhea sintenisii*, Ébano verde (*Magnolia pallescens*), *Cleyera bolleana, Juglans jamaicensis* (VU), *Podocarpus aristulatus* (VU), *Cyathea spp., Vanilla wrightii,* Palo de viento *(Didymopanax tremulus),* Manacla *(Prestoea montana), Pleodendron ekmanii, Tabebuia bullata y T. vinosa* (León y Arias,

[3] http://ambiente.gob.do/wp-content/uploads/2016/10/Reserva-Cientifica-Ebano-Verde
[4] http://www.grupojaragua.org.do/documents/AICAS/DR-IBAS_2010_DO012_Ebano_Verde.pdf

2009, cit. Perdomo et al., 2010) También son importantes las especies (sin nombre común) *Pinguicola casabitoana, Gonocalyx tetraptera, Lyonia alaini, Gesneria sylvicola y Myrcia saliana,* Jaiquí *(Bumelia salicifolia),* Tárana *(Linociera caribaea),* Pino criollo *(Pinus occidentalis),* Palo santo *(Alpinia speciosa),* Sangre de pollo *(Mecranium amigdalinum*), entre otras.

Figura 3. Bosque ribereño en Reserva Científica Ébano Verde (RCEV)[5]

Fauna.

Avifauna: En la RCEV se han reportado aproximadamente 93 especies de aves (BirdLife International y Grupo Jaragua, 2006b) y de la Sociedad Ornitológica de la Hispaniola (2006). Este area es crítico para especies endémicas tales como el chirrí *(Calyptophilus frugivorus*) y el papagayo *(Priotelus roseigaster*), consideradas Vulnerable (VU) y Casi Amenazada (NT), respectivamente, según la Lista Roja de la Unión Mundial para la Naturaleza (UICN). Este IBA también es hábitat de especies de distribución limitada en el territorio nacional tales como la Cigüita de Constanza *(Zonotrichia capensis)* (Perdomo et al., 2010).

Tachycineta euchrysea VU	*Todus subulatus*
Xenoligea montana VU	*Nesoctites micromegas*
Calyptophilus frugivorus VU	*Melanerpes striatus*
Priotelus roseigaster NT	*Elaenia fallax*
Corvus palmarum NT	*Contopus hispaniolensis*
Geotrygon leucometopia VU	*Myiarchus stolidus*
Coccyzus longirostris	*Vireo nanus*
Tyto glaucops	*Dulus dominicus*
Anthracothorax dominicus	*Myadestes genibarbis*
Chlorostilbon swainsonii	*Carduelis dominicensis*
Mellisuga minima	*Microligea palustris*
Todus angustirostris	*Phaenicophilus palmarum*
Euphonia musica	

Tabla 1. Especies de aves amenazadas en la RCEV. (Perdomo et al., 2010)

Nota: VU = Vulnerable; NT = Casi Amenazada

Anfibios y otros: Esta reserva constituye un hábitat muy adecuado para la mayoría de las especies de anfibios. (SEA/DVS ,1992a y León y Arias ,2009, cit. Perdomo et al., 2010) reportan la rana arborícola gigante de La Española *(Osteopilus vastus),* reportada en peligro (EN) según la UICN, así como la rana arborícola gigante *(Hypsiboas heilprini*, VU), la rana de los arroyos del norte *(Eleutherodactylus schmidti*, CR), la rana martillo del norte *(E. auriculatoides*, EN), la rana sollozante de La Española *(E. minutus*, EN) y la rana melodiosa de La Española *(E. pituinus,* EN) (SEA/DVS, 1992a, León y Arias 2009, cit. Perdomo et al., 2010).

Además se reportan 10 especies de reptiles, entre ellas el lagarto *Anolis insolitus* considerado como muy raro. En la RCEV se reporta la presencia del Solenodonte *(Solenodon paradoxus*) mamífero endémico, considerado

[5] https://www.gestiopolis.com/analisis-ambiental-reserva-ebano-verde-republica-dominicana/

EN. También se reportó la presencia del pez endémico Poecilia dominicensis en los ríos y arroyos que nacen en esta Reserva. Además se ha identificado una variada fauna de insectos que incluye 9 órdenes y 25 familias. Entre los grupos destacados se hallan las mariposas, con 9 géneros, que incluye la mariposa de alas de cristal *(Greta diaphana),* indicadora de zonas de vida de altura (Perdomo et al., 2010).

Amenazas a la Biodiversidad

Entre las principales amenazas en el área, según el Programa Nacional de Valorización de Áreas Protegidas (SEMARENA, 2004, cit. Perdomo et al., 2010) están: las especies de flora y fauna introducidas y/o invasoras, la ganadería, los incendios forestales provocados, la extracción y tráfico de madera y la captura de aves juveniles y pichones. Algunos expertos consideran que la destrucción o modificación de los hábitats naturales para la ampliación de las fronteras agrícola y urbana son las amenazas actuales más importantes. Otro impacto importante ha sido la invasión de helechos en zonas deforestadas y erosionadas, los cuales forman una densa cobertura que no permite la regeneración del bosque original (Slocum et al., 2004; 2000,cit. Perdomo et al., 2010). Estos helechales están conformados principalmente por *Dicranopteris pectinata*, mezclado con *Gleichenia bifida* y *Pteridium aquilinum*.

Bibliografía

- Perdomo, L., Y. Arias, Y. Léon y D. Wege. (2010). Áreas Importantes para la Conservación de las Aves en la República Dominicana. Grupo Jaragua y el Programa IBA-Caribe de BirdLife International: República Dominicana. Reserva Científica Ébano Verde. http://www.grupojaragua. org.do /documents/AICAS/DR-IBAS_2010_ DO012_Ebano_ Verde. Pdf.
- Viceministerio de Áreas Protegidas y Biodiversidad. (2017). Informe técnico interno. Reserva Científica Ébano Verde.

RESERVA CIENTÍFICA DICAYAGUA

Creación: 7 de agosto de 2009, mediante el Decreto No. 571-09

Administración: Ministerio de Medio Ambiente y Recursos Naturales

Categoría: Área de Protección Estricta

Ubicación: La reserva está localizada al sur-suroeste de la ciudad de Santiago de los Caballeros. Se encuentra dentro de una zona de vida de Bosque seco Subtropical (Bs-S) y abarca una superficie de 1.15 kilómetros cuadrados a lo largo de una sección del río Dicayagua, afluente del Yaque del Norte.[6] Tiene la categoría I (Área de Protección Estricta) según la Ley 202-04 que corresponde con la categoría 1a (Reserva Natural Estricta) de la UICN. Coordenadas asociadas: 19° 24′ 09″ N – 70° 46′ 03″ O.[7]

Figura 4. Ubicación de la Reserva Científica Dicayagua[6,8]

Topografía, hidrología, clima y paisajes.

Se crea la Reserva Científica Dicayagua con el propósito de conservar una muestra muy singular, probablemente la única o la más expresiva del territorio nacional, de cactáceas epifitas sobre especies arbóreas ribereñas, donde se observa el fenómeno botánico-fisiológico poco común de Cayucos (*Cereus sp.)* y Pitajayas (Hylocereus sp.), entre otros cactus, creciendo o desarrollándose sobre el Samán (*Pytecelobium saman*) y otros árboles corpulentos en las márgenes del rio Dicayagua .

Figura 5. Bosque Ribereño con cactáceas en la Reserva Científica Dicayagua[9]

[6] https://jmarcano.com/ecohis/areas/categoria1/dicayagua.html
[7] Idem
[8] http://ambiente.gob.do/wp-content/uploads/2016/10/Reserva-Cientifica-Dicayagua.pdf
[9] https://web.facebook.com/foroap/posts.

Nota: no hay otras informaciones disponibles a partir de las fuentes consultadas.

RESERVA CIENTÍFICA VILLA ELISA

Creación: 6 de abril de 1976 (Decreto No. 1863). Ratificada por Decreto 571-09 Ley 202-04
Administración: Ministerio de Medio Ambiente y Recursos Naturales
Categoría: Área de Protección Estricta

Ubicación: La Reserva Científica Villa Elisa está localizada 8 km al norte del poblado de Villa Elisa, en la provincia de Monte Cristi, municipio de Guayubín, provincia Montecristi, entre las coordenadas geográficas 19º 30' 12" Latitud Norte y 71º 30' 15" Longitud Oeste. y fue declarada como tal mediante el Decreto No. 1863 del 6 de abril de 1976; posteriormente, el Decreto 176-86 la nombró "Dr. Orlando Cruz Franco" y redujo la superficie a 113.4 tareas (7.09 hectáreas). La Ley 64-00 sobre Medio Ambiente y Recursos Naturales ratificó los términos del Decreto 1863-76 y fue confirmada por la Ley Sectorial de Áreas Protegidas del año 2004. Tiene la categoría I (Área de Protección Estricta) según dicha ley, lo que corresponde con la categoría 1a (Reserva Natural Estricta) de la UICN. Se señala que actualmente tiene una superficie de 234,000 metros cuadrados.[10] Fue declarada reserva científica con el objetivo de proteger una de las más raras especies de orquídea de nuestra flora, *Tolumnia henekenii* (= *Oncidium henekenii*), conocida como "Cacatica".[11,12]

Figura 8. Ubicación de la Reserva Científica Villa Elisa.[13]

Topografía, hidrología, clima y paisajes

La zona es llana, con una pequeña elevación en el lado noroeste. Sus suelos son de origen sedimentario y están formados de partículas finas de color gris oscuro o amarillento en algunas partes., a una altitud de 120 msnm. Se encuentra dentro de la zona de vida Bosque seco Subtropical (Bs-S). Antes de ser declarada reserva científica, una parte del lugar estuvo dedicada a cultivos, ganadería y al corte de árboles para carbón. Como consecuencia de estas actividades, su vegetación está compuesta de árboles pequeños, arbustos, hierbas y enredaderas, principalmente en la parte nordeste. Aproximadamente el 90% de los terrenos circundantes están dedicados a la agricultura y la ganadería, mayormente a la crianza de cabras y ovejas. La vegetación en esas parcelas ha sido eliminada, quedando algunos árboles usados como sombra para el ganado.[14]En el lado oriental del área protegida existe una extensión de aproximadamente 10 tareas que constituyen un vestigio de la vegetación original de la zona.

[10] https://jmarcano.com/ecohis/areas/categoria1/velisa.html
[11] Idem
[12] http://www.ecoportaldominicano.org/puntos-a-visitar/areas-protegidas/la-reserva-cientifica-villa-elisa/
[13] http://ambiente.gob.do/wp-content/uploads/2016/10/Reserva-Cientifica-Villa-Elisa
[14] https://jmarcano.com/ecohis/areas/categoria1/velisa.html

Dentro del territorio que comprende esta unidad, no existen corrientes superficiales de agua y las condiciones climáticas se caracterizan por días claros y soleados durante los meses en que no llueve y parcialmente nublados durante la época de lluvias y los meses de enero a marzo. Las precipitaciones varían desde 545 mm hasta 980 mm al año. La temperatura media anual para esta zona de vida es de 22.5 °C.

Figura 9. (Izq.)Bosque seco Subtropical (Bs-S) en Reserva Científica Villa Elisa. (Der.) Flor de la Cacatica (*Tolumnia henekenii*), una de las más raras especies de orquídeas del país.[15]

Flora

La flora de la reserva, establece la existencia de 138 especies, 28 de las cuales son endémicas de la Isla Hispaniola, 104 son nativas y tres son introducidas y/o naturalizadas. El estrato arbóreo está conformado por las especies Almácigo o Indio Desnudo, Frijolillo, Alpargata, Cayuco, Orquídeas y las Bromeliáceas, son dominantes dentro del grupo de las epifitas; se excluyen las siete (7) especies de orquídeas entre las cuales se destaca una de las más raras de nuestra flora que es la *Tolumnia Henekenii*, popularmente denominada "Cacatica". El estrato inferior está formado por hierbas, siendo los géneros más comunes: Setaria, Acaleypha y Spermacoce. [16]

La parte nordeste de la reserva está cubierta por una vegetación secundaria, en donde se destacan el Cambrón, el Guayacán, estos últimos señalan el restablecimiento del bosque original; otras cactáceas importantes son Bombillito y Tuna Brava. Aparecen además, las siguientes especies: Palo de Hierro o Quiebra de hacha, Saona, Baitoa y Vera. Fue declarada reserva científica con el objetivo de proteger una de las más raras especies de orquídea de nuestra flora, Tolumnia henekenii (=Oncidium henekenii), conocida como "Cacatica". Las poblaciones de esta orquídea fueron reducidas considerablemente debido a la tala del bosque para hacer carbón y labores agrícolas, así como la comercialización ilegal de la "cacatica". En el lado Este del área protegida existe una extensión de aproximadamente 10 tareas que constituyen un vestigio de la vegetación original de la zona.[17,18]

Fauna

La avifauna asociada a la vegetación de la Reserva Científica de Villa Elisa, está caracterizada por la presencia de especies tales como: Rey Congo, Cuyaya o Cernícalo, Tórtola, Petigre, Zumbador, Barrancolí, Canario, Rolita y Cotorra.[19]

Amenazas a la Biodiversidad

Parte de esta reserva científica, estuvo dedicada a cultivos, ganadería y al corte de árboles para carbón. Como consecuencia de estas actividades, su vegetación está compuesta de árboles pequeños, arbustos, hierbas y enredaderas, principalmente en la parte nordeste. Por lo que la destrucción de las formaciones vegetales nativas del lugar, con fines agrícolas y de ganadería, comercialización de especies de orquídeas nativas, entre otras son las principales amenazas.

---

[15] https://jmarcano.com/ecohis/areas/categoria1/velisa.html
[16] https://sistemasdeareasprotegidas.es.tl/Reserva-Cient%EDfica-De-Villa-Elisa.htm
[17] Idem
[18] http://www.ecoportaldominicano.org/puntos-a-visitar/areas-protegidas/la-reserva-cientifica-villa-elisa/
[19] https://jmarcano.com/ecohis/areas/categoria1/velisa.html

Bibliografía: Ver pie de paginas

PARQUE NACIONAL ARMANDO BERMÚDEZ

Creación: Ley N.º 4389 del 19 de febrero de 1956

Administración: Ministerio de Medio Ambiente y Recursos Naturales

Categoría: Parque Nacional

Ubicación: El Parque Nacional Armando Bermúdez está situado en la vertiente Norte y en la parte central de la Cordillera Central, entre las coordenadas geográficas 19° 17' - 18° 52' latitud Norte, y los 71° 27' - 70° 46' longitud Oeste; esto es su ubicación junto al Parque Nacional José del Carmen Ramírez, con una extensión de 766 km². [20] Este Parque Nacional fue declarado como tal mediante la Ley No. 4389 del 19 de febrero de 1956. Está situado en la vertiente norte y en la parte central de la Cordillera Central. El PNAB, se extiende, de Este a Oeste, desde La Ciénaga de Manabao, en la provincia La Vega, hasta el Parque Nacional Nalga de Maco, en la parte alta de la cuenca del río Artibonito. Por su límite norte, el parque limita con las comunidades de Mata Grande, en la provincia de Santiago, La Diferencia, Los Ramones, Lomita y La Cidra, en Santiago Rodríguez, mientras que, por su lado sur, colinda con el Parque Nacional José del Carmen Ramírez.[21]

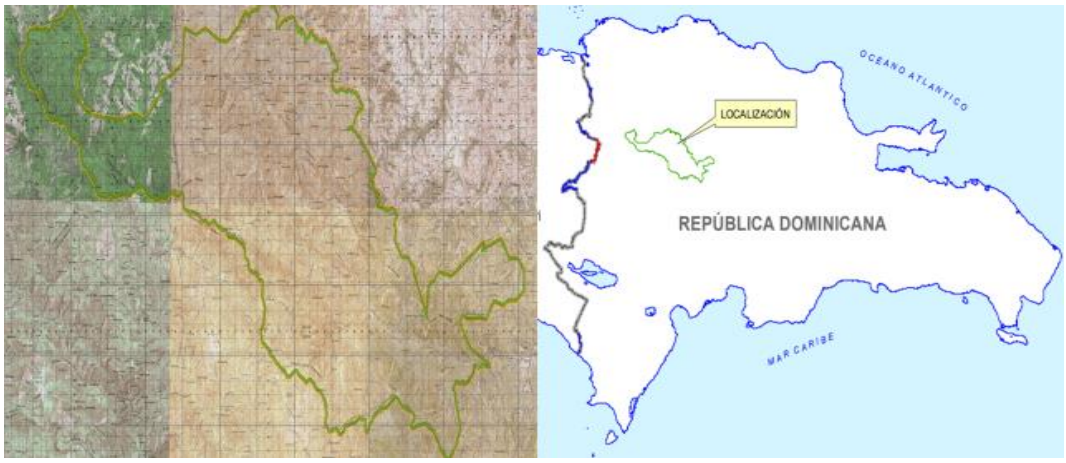

Figura 10. Ubicación del Parque Nacional Armando Bermúdez en la Cordillera Central[22]

Topografía, hidrología, clima y paisajes

Todas las cuencas ubicadas en los territorios del Parque Nacional Armando Bermúdez (PNAB) drenan sus aguas a la Cuenca del Río Yaque del Norte, el cual presenta en la estación de Palo Verde donde ya ha recibido todos sus afluentes un caudal promedio de 66.5 m3/s. En el Parque Nacional Armando Bermúdez las precipitaciones anuales varían entre 1000 y 2000 mm. Estos valores tienden a ir aumentando de Norte a Sur. En relación con la temperatura los valores medios anuales son de 18°C, pudiéndose registrar en algunos lugares, especialmente en las sabanas intramontanas, temperaturas bajo 0°C.[23] (SEMARN, 2004; Perdomo et al., 2010)

Las zonas de vida que se encuentran en este Parque Nacional son Bosque húmedo Montano Bajo (Bh-MB) y Bosque muy húmedo Montano Bajo (Bmh-MB); en algunos lugares, puede encontrarse la zona de vida Bosque pluvial Montano Bajo (Bp-MB) donde reina una alta humedad y existen especies características de esta zona de vida como la Manacla (*Prestoea montana*) y los helechos arborescentes. [24] El relieve es abrupto y comparte con el Parque Nacional José del Carmen Ramírez la mayor altura de las Antillas representado por

[20] https://jmarcano.com/ecohis/areas/categoria2/bermudez.html
[21] Idem
[22] http://ambiente.gob.do/wp-content/uploads/2016/10/Parque-Nacional-Armando-Bermudez.pdf
[23] https://jmarcano.com/ecohis/areas/categoria2/bermudez.html
[24] Idem

el pico Duarte, con una altura de 3,175 metros, seguido por los picos La Pelona (3,097 metros), Yaque (2,760 metros) y La Rusilla (3,038 metros).

Junto con el Parque Nacional José del Carmen Ramírez, este Parque Nacional comprende alrededor de unos 12 ríos principales del país, comprendiendo las cuencas altas de los ríos Yaque del Norte, Jagua, Bao, Ámina, Guayubín y de todos sus afluentes. En los meses de diciembre y enero la cuando la temperatura desciende por debajo de 0 °C durante la madrugada, los "pajones" se cubren de escarcha. Los niveles más bajos de temperatura se registran en el Valle del Tetero, el Valle de Bao y en Macutico. El Parque se encuentra en una zona de alta precipitación, teniéndose registros entre 1,000 y 3,500 mm; es posible que en algunos lugares las precipitaciones estén por encima de los 4,000 mm de lluvia.[25] (SEMARN, 2004).

Figura 11. Vistas del Parque Nacional Armando Bermúdez[26],[27]

Flora

Estudios realizados en el área reportan unas 786 especies de plantas incluidos los helechos, de las que 186 son endémicas de la República Dominicana, lo que representa un 35% de las especies reportadas. Se pueden definir cuatro pisos boscosos de acuerdo a la altura: máximo, superior, intermedio y bajo. En el primer piso predomina el Pino criollo, la especie endémica Pinus occidentalis; en el segundo, se distinguen el Yagrumo (Cecropia peltata), Cedro *(Cedrela odorata*), Nogal *(Juglans jamaicensis*), Palma manacla *(Prestoea montana*), Rabo de vaca *(Tropis racemosa),* Penda *(Citharexylum fruticosum)* y Capá *(Petitia domingensis).* En el piso intermedio destacan: Copey *(Clusia rosea),* Pino de teta *(Zantophylum spinifex)*, Gri-grí *(Bucida buceras)* y Palo amargo *(Trichilia pallida*). En el piso bajo predominan Guayuyo (*Piper adumcum) y* Aceituno *(Prunus myrtifolia).* El área también es rica en helechos, epífitas y arbustos. (Perdomo et al., 2010).

En este parque, 17 especies de plantas vasculares están consideradas amenazadas. Entre estas figuran: *Agave intermixta, Calyptronoma rivalis, Penelopeia suburceolata, Illicium ekmanii, Cedrela odorata, Wallenia apiculata, Pimenta ozua, Podocarpus hispaniolensis, Coccoloba fuertesii, Pouteria sessiflora, las orquídeas Anacheilium vespum, Comparettia falcata, Dichaea swartzii, Epidendrum paranaense, Malaxis unifolia, Oncidium tuerckheimii y Stelis domingensis.* Entre las plantas de más alto valor de conservación, podemos mencionar además, las dos especies de Podocarpus *(P. aristulatus y P. hispaniolensis), Solanum coelocalix, S. orthacantum*, Palo de viento *(Didymopanax tremulus),* helechos arborescente *(Cyathea spp.), asi como Tabebuia vinosa, T. bullata, Tillandsia moscosoi*, Palma manacla *(Prestoea montana)* y *Lyonia spp*, (SEMARN, 2004; Perdomo et al. 2010).

No.	**Tipo de uso y cobertura**	**Km²**	Porcentaje
1	Bosque de pinos	208.00	27.12 %
2	Bosque nublados	74.20	9.67 %
3	Bosque latifoliado húmedo	70.50	9.19 %
4	Uso agrícola, ganadero y agroforestal (café)	414.00	53.99 %

[25] https://jmarcano.com/ecohis/areas/categoria2/bermudez.html
[26] https://ambiente.gob.do/author/webmaster/page/5/

[27] https://mapio.net/pic/p-47379210/

	Total	**766.70**	100.00 %

Tabla 3. Cobertura boscosa del Parque Nacional Armando Bermúdez (SEMARN, 2004)

Fauna

Según León y Arias ,2009 cit. Perdomo et al., (2010), en este Parque Nacional, se encuentran 11 especies de anfibios endémicos amenazados. Los reptiles endémicos están representados por los lagartos anolinos *Anolis etheridge, A. fowlery, A. schrebey* y los ánguidos *Celestus marcanoi y C. darlingtoni*. Además, alberga a dos mamíferos endémicos y en Peligro de extinción (EN), el Solenodonte *(Solenodon paradoxus)* y la Jutía *(Plagiodontia aedium)*. En la localidad se han reportado algunos insectos únicos, tales como la Mariposa Lucerito *(Calisto spp.),* el Saltamonte de Duarte (*Duartetis spp.)* y el Escarabajo de alas pectinadas *(Sarifer seabrai)*. La avifauna del PNAB está compuesta por aproximadamente 104 especies.

El PNAB es un hábitat crítico para poblaciones de especies de avifauna endémicas amenazadas, actualmente comunes sólo en reservas boscosas. Tal es el caso del Perico (*Aratinga chloroptera)* y la Cotorra *(Amazona ventralis),* ambas en estado Vulnerable (VU) de acuerdo a la Unión Mundial para la Naturaleza (UICN). También, alberga especies de distribución restringida como el Papagayo o Trogón *(Priotelus roseigaster),* Cigüita aliblanca (*Xenoligea montana)* y el Pico cruzado *(Loxia megaplaga),* asociadas a bosques de montaña y pinares. Estas especies son consideradas como "casi amenazadas" (NT), vulnerables (VU) y en peligro (EN) de extinción, respectivamente, por la UICN. El PNAB también sirve de refugio a una variedad de especies migratorias invernales, entre ellas se encuentra el Zorzal de Bicknell *(Catharus bicknelli),* considerada VU (Sociedad Ornitológica de la Hispaniola, 2006, cit. Perdomo et al., 2010).

Turdus swalesi	*EN*	*Chlorostilbon swainsonii*	*n.e.*
Loxia megaplaga	*EN*	*Mellisuga minima*	*n.e.*
Aratinga chloroptera	*VU*	*Todus angustirostris*	*n.e.*
Amazona ventralis	*VU*	*Todus subulatus*	*n.e.*
Corvus leucognaphalus	*VU*	*Nesoctites micromegas*	*n.e.*
Tachycineta euchrysea	*VU*	*Melanerpes striatus*	*n.e.*
Xenoligea montana	*VU*	*Elaenia fallax*	*n.e.*
Calyptophilus frugivorus	*VU*	*Contopus hispaniolensis*	*n.e.*
Siphonorhis brewsteri	*NT*	*Myiarchus stolidus*	*n.e.*
Priotelus roseigaster	*NT*	*Dulus dominicus*	*n.e.*
Corvus palmarum	*NT*	*Myadestes genibarbis*	*n.e.*
Catharus bicknelli	*VU*	*Carduelis dominicensis*	*n.e.*
Coccyzus longirostris	*n.e.*	*Microligea palustris*	*n.e.*
Tyto glaucops	*n.e.*	*Phaenicophilus palmarum*	*n.e.*
Caprimulgus ekmani	*n.e.*	*Euphonia musica*	*n.e.*
Anthracothorax dominicus	*n.e.*		

Tabla 4. Especies de aves amenazadas. Parque Nacional Armando Bermúdez (Perdomo et al., 2010).

Nota: EN= en peligro; VU= vulnerables; NT= casi Amenazadas; n.e. = no especificado

Amenazas a la Biodiversidad

Las principales amenazas que enfrenta el lugar son el avance de la frontera agrícola y ganadera, la extracción de madera a pequeña escala (de subsistencia), las especies introducidas y/o invasoras como cerdos y la cacería, principalmente de colúmbidos. Los incendios forestales provocados generan pérdida de flora y fauna del lugar. También se menciona una grave erosión y presencia de desechos sólidos en los senderos de caminatas. Otra amenaza inminente son las propuestas de desarrollo de infraestructura para producción de energía hidroeléctrica (represas o embalses), (Perdomo *et al*., 2010).

Bibliografía

- Perdomo, L., Y. Arias, Y. Léon y D. Wege. (2010). Áreas Importantes para la Conservación de las Aves en la República Dominicana. Grupo Jaragua y el Programa IBA-Caribe de BirdLife International:

República Dominicana. Santo Domingo. Parque Nacional Armando Bermúdez. http://www. Grupojaragua .org .do/documents/AICAS/DR-IBAS_2010_DO003_ Armando_Bermudez.pdf

- SEMARN (2004). Secretaría de Estado de Medio Ambiente y Recursos Naturales: Plan de Manejo del Parque Nacional Armando Bermúdez. Versión Corta. Santo Domingo, República Dominicana. Diciembre 2004. http://www.ilustrados.com/tema/9410/Plan-manejo-Parque-Nacional-Armando-Bermudez.html

PARQUE NACIONAL BAIGUATE

Creación: Fue creado mediante el Decreto 571-2009.

Administración: Ministerio de Medio Ambiente y Recursos Naturales

Categoría: Parque Nacional

Ubicación: El Parque Nacional Baiguate, está ubicado en el municipio de Jarabacoa, provincia La Vega, en la Cordillera Central, entre las coordenadas 328534 mE, 2103004 mN. al sur del municipio de Jarabacoa, aproximadamente a 3.75 kilómetros. Posee una extensión territorial de unos 52.44 kilómetros cuadrados. Categoría II-UICN (Ministerio de Medio Ambiente y Recursos Naturales, 2017). Se crea el Parque Nacional Baiguate**,** con el propósito de conservar las inmensas alfombras de pinos y los hermosos bosques de galería (mixtos y latifoliados) que se conjugan en el curso medio de este río, donde todavía aparece el Nogal como especie testigo o indicadora del bosque original, actualmente muy amenazada y que debe ser rescatada por gran valor forestal y cultural; de igual manera se le brinda protección al legendario Salto Baiguate, sitio de baño y la celebración de ritos especiales y propios de la cultura taína asentada en esta parte de la isla.[28]

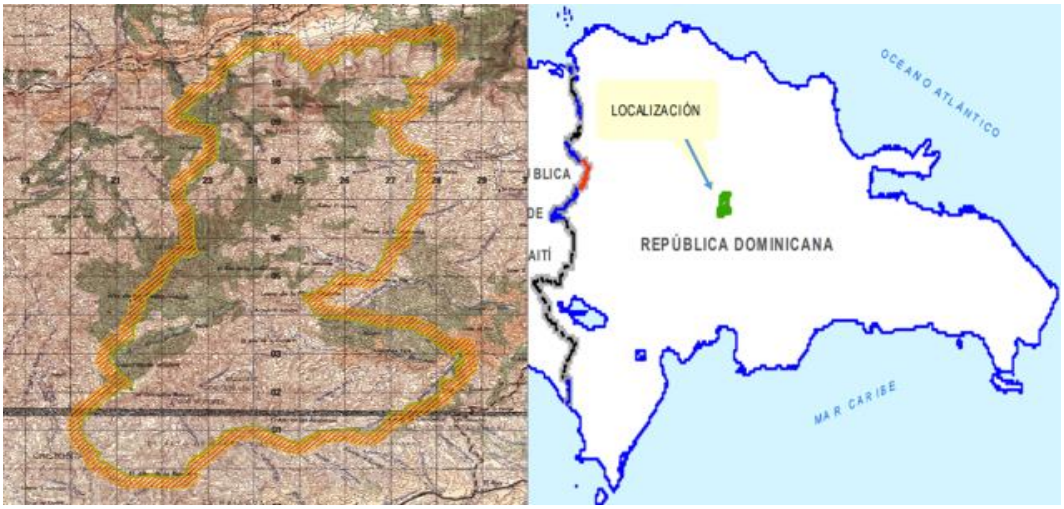

Figura 12. Ubicación del Parque Nacional Baiguate, en la Cordillera Central[29]

[28] https://www.accionverde.com/parque-nacional-baiguate/

[29] http://ambiente.gob.do/wp-content/uploads/2016/10/Parque-Nacional-Baiguate

Figura 13. Bosque ribereño y bosque latifoliado húmedo del Parque Nacional Baiguate[30]

Topografía, hidrología, clima y paisajes

La gran red hidrográfica del área es influenciada por la configuración de la topografía escarpada y la alta incidencia de las lluvias caídas en la zona, con pluviometría media anual que alcanza los 2,000 mm. La principal fuente hidrológica está representada por el río Baiguate, el cual nace en el extremo sureste de la zona montaña correspondiente a El Alto de la Bandera a una altura de 1,804 metros. Esta zona presenta un clima tropical lluvioso; con una temperatura promedio anual de 22 °C y lluvias abundantes durante casi todo el año. El Parque Nacional Baiguate se ubica en el área de la Cordillera Central, representada geomorfológicamente por zona definitivamente montañosa, con topografía muy accidentada y pendientes muy escarpadas que varían de 50 – 70 %, bordeando el valle de Jarabacoa. Los principales ecosistemas presentes en el Parque son: 1) río, 2) bosque ribereño, 3) bosque latifoliado húmedo, 4) pastos, 5) áreas reforestadas, 6) Pino Cuaba. (Ministerio de Medio Ambiente y Recursos Naturales. 2017).

Flora. Principales ecosistema presentes: Bosque ribereño, Bosque de Pino cuaba y Matorrales (Ministerio de Medio Ambiente y Recursos Naturales, 2017).

Nombre común	Nombre científico	Nivel de amenaza*
Maguey	*Agave antillarum*	EN
Palo de viento	*Schefflera tremula*	CR
Manacla	*Prestoea montana*	VU
Yaguasa	*Tabebuia bullata*	EN
Roble	*Tabebuia. vinosa*	EN
Barba de viejo	*Tillandsia usneoide*	VU
Sin nombre común	*Dichaea sp.*	EN
Sin nombre común	*Pleurothallis sp.*	EN
Sin nombre común	*Tolumnia sp.*	EN
Sin nombre común	*Tolumnia variegata*	VU
Sin nombre común	*Tolumnia tuerckheimii*	CR

Tabla 5. Especies de plantas amenazadas del Parque Nacional Baiguate
Nota: EN= en peligro; VU= vulnerables; NT= casi Amenazadas; CR= Peligro Critico

USO Y COBERTURA	SUPERFICIE (Km²)	PORCENTAJE (%)
Bosque latifoliados Húmedos	31.19	59.49
Matorrales	6.68	12.74
Pasto / Agricultura	13.82	26.36
Plantación Forestal (Pino)	0.13	0.25
Proyectos Inmobiliarios	0.61	1.16
Total General	**52.43**	**100.00**

Tabla 6. Descripción, usos y cobertura del suelo

Fauna

En el Parque Nacional Baiguate se observaron cuatro (4) géneros y 19 especies de anfibios, representados por las familias: Bufonidae, Eleutherodactylidae, Hylidae y Ranidae; más 12 géneros y 28 especies de reptiles,

[30] https://www.tripadvisor.es/Attraction_Review-g675009-d3440196-Reviews-Baiguate_ Salto_ Waterfall-Jarabacoa_La_Vega

representados por las familias: Amphisbaenidae, Anguidae, Dactyloidae, Gekkonidae, Leiocephalidae, Sphaerodactylidae, Teiidae, Boidae, Dipsadidae, Tropidophiidae, Typhlopidae y Emydidae. De las 19 especies de anfibios, 17 son endémicas y dos (2) introducidas, para un 41% de la especies endémicas, 11 se encuentran amenazada (Ministerio de Medio Ambiente y Recursos Naturales, 2017). En el caso de los reptiles de las 28 especies presentes en el área, siete (7) se encuentran en algún grado de amenazas, para un 10% de las especies amenazadas, 25 son endémicas, dos (2) nativas y una (1) introducida, para un 24% de endemismo y un 25% de las especies de reptiles reportados para la República Dominicana.

Para el Parque Nacional Baiguate, se reportan en la actualidad un total de 44 especies de aves, distribuidas en 24 familias. De ese total de especies, 23 son residentes, 15 endémicas, equivalente a 47% de las 32 reportadas para la Isla La Española, cuatro (4) migratorias, una (1) introducida y una (1) colonizadora. (Ministerio de Medio Ambiente y Recursos Naturales, 2017).

Nombre común	Nombre científico	Nivel de amenaza*
Paloma ceniza	*Patagioenas inornata*	Vulnerable
Cotorra	*Amazona ventralis*	En Peligro
Perico	*Corvus leucognaphalus*	En Peligro
Cao	*Corvus palmarum*	En Peligro
Cuervo	*Corvus leucognaphalus*	En Peligro
Cigüita de pinar	*Setophaga pinus*	Vulnerable

Tabla 7. Especies de aves amenazadas en el Parque Nacional Baiguate

Nombre común	Nombre científico	Nivel de amenaza*
Sapo crestado sureño	*Peltophryne guentheri*	Vulnerable
Rana martillo del norte	*Eleutherodactylus auriculatoides*	En Peligro
Rana grillo de la montaña	*Eleutherodactylus haitianus*	En Peligro
Rana sollozante de la Hispaniola	*Eleutherodactylus minutus*	En Peligro
Rana de la montaña de Hispaniola	*Eleutherodactylus montanus*	En Peligro
Rana de la Cordillera Hispaniola	*Eleutherodactylus patriciae*	En Peligro
Rana melodiosa de la Hispaniola	*Eleutherodactylus pituinus*	En Peligro
Rana de los arroyos del Norte	*Eleutherodactylus schmidti*	Peligro Critico
Rana arborícola verde Hispaniola	*Hypsiboas heilprini*	Vulnerable
Rana arborícola amarilla Hispan.	*Osteopilus pulchrilineatus*	En Peligro
Rana arborícola gigante Hispaniola	*Osteopilus vastus*	En Peligro
Anolis gigante de Dominicana	*Anolis baleatus*	En Peligro
Anolis del tronco abanico grande	*Anolis christophei*	En Peligro
Anolis de los arbustos de montaña	*Anolis etheridgei*	En Peligro
Anolis de bandas verde	Anolis fowleri	Peligro Critico
Anolis de las ramitas de la Cordillera Central	*Anolis insolitus*	En Peligro
Corredora verde de la Hispaniola	*Hypsirhynchus melanichnus*	Peligro Critico
Jicotea norteña	*Trachemys stejnegeri*	Vulnerable

Tabla 8. Especies de anfibios y reptiles amenazados, del Parque Nacional Baiguate

Nota: EN= en peligro; VU= vulnerables; NT= casi Amenazadas

Amenazas a la Biodiversidad

La agricultura y la ganadería en el interior del parque y en la zona periférica, presentes desde antes de crearse el área protegida; la construcción de infraestructuras para vivienda y desarrollo de actividades turísticas y plantaciones forestales con fines de explotación.

Bibliografía consultada

- Ministerio de Medio Ambiente y Recursos Naturales. 2017. Plan de manejo del Parque Nacional Baiguate. Santo Domingo RD. https://ambiente.gob.do/transparencia/download/329/plan-de-manejo/735/plan-de-manejo-parque-nacional-de-baiguate.pdf

PARQUE NACIONAL JOSÉ DEL CARMEN RAMÍREZ

Creación: Fue creado mediante la Ley 5066 del 24 de diciembre de 1958. Ley 202-04, decreto 571-09.

Administración: Ministerio de Medio Ambiente y Recursos Naturales

Categoría: Parque Nacional

Ubicación: Se encuentra en la vertiente sur de la Cordillera Central, limitando al Sur y al Este con las provincias Azua y San Juan de la Maguana, al Norte con el Parque Nacional Armando Bermúdez, al Oeste con los municipios de Jarabacoa y Constanza, ambos de la provincia de La Vega. Posee un territorio de 764 km².

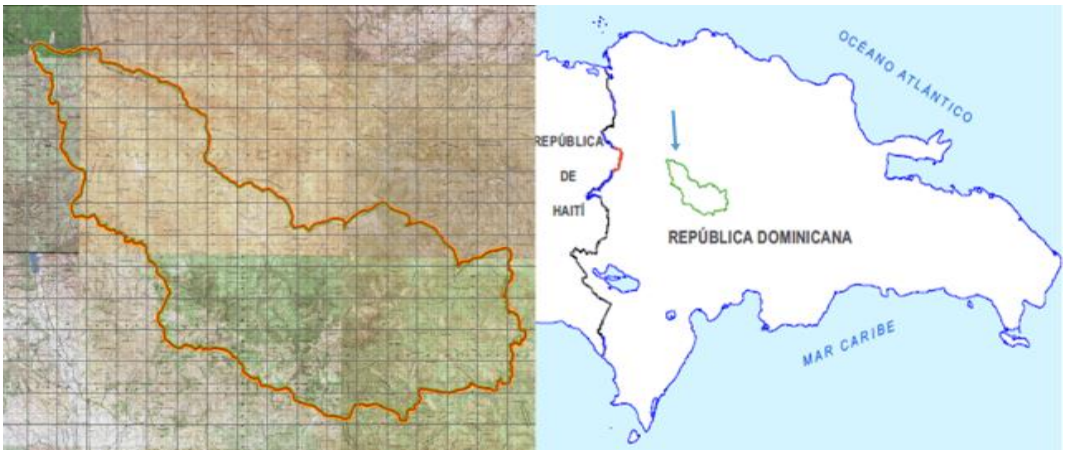

Figura 14. Ubicación del Parque Nacional José del Carmen Ramírez[31]

Topografía, hidrología, clima y paisajes:

Aquí nacen los principales ríos que producen la irrigación del Valle de San Juan; el principal es el río Yaque del Sur. Las principales cuencas protegidas por este parque son las de los ríos Yaque del Sur, San Juan y Mijo, incluyendo sus afluentes.

La precipitación en el interior del parque es de 900 mm en sus zonas más bajas, 1,800 a 2,300 mm en elevaciones medias (cuencas de recepción de los ríos San Juan y Mijo) y 1,200 mm en las zonas más elevadas. Los niveles de temperatura oscila en función de altitud, y en las partes altas son frecuentes rango de 12° a 18 °C. En general, la pluviometría imperante es de alrededor de 2,500 mm anuales de lluvias, confiriéndole la característica de bosque húmedo subtropical (SEMARN ,2005).

El PNJCR consiste de áreas de montaña y valles intramontanos. Este parque comprende una vasta porción de la vertiente sur de la Cordillera Central y en él se localiza el punto más alto de las Antillas, el pico Duarte con 3,175 metros; y comparte con el Parque Nacional Armando Bermúdez otras elevaciones no menos importantes como son los picos Yaque, La Rusilla y La Pelona. La mayor parte del PNJCR se encuentra cubierto por ecosistemas de Pino y mixtos (pino - latifoliado), los cuales se desarrollan desde áreas altas de los cimas de la Cordillera Central como el Pico Duarte y la Rucilla hasta las áreas más bajas en las zonas limítrofes del PNJCR. El pino (Pinos occidentalis) es la especie arbórea más abundante, la cual confiere al paisaje una aparente identificación fisonómica. En el área existen 508.9 km^2 con cobertura de bosque de pino (68,9%). Un área aproximadamente de 203.5 km^2 (27,6%) del parque ha sido afectado en su cobertura boscosa a causa de

[31] http://ambiente.gob.do/wp-content/uploads/2016/10/Parque-Nacional-Jose-Carmen-Ramirez.pdf

las actividades de ganadería, agricultura y el cultivo del café desarrolladas antes de la declaratoria como área protegida. (SEMARN ,2005).

Figura 15. Áreas de montaña y valles intramontanos del Parque Nacional José del Carmen Ramírez. Se observa la cobertura de Bosque de Pino (Izquierda).[32]

No.	Uso y cobertura	km^2	%
1	Bosque de pinos	508.9	68.9 %
2	Bosque Húmedos	25.42	3.4 %
3	Bosque mixto	96.43	13.1 %
4	Praderas	5.3	0.72 %
5	Agricultura y ganadería	101.75	13.8 %
	Total	**737.8**	**100 %**

Tabla 9. Cobertura Boscosa del Parque Nacional José del Carmen Ramírez (SEMARN , 2005)

Flora.

La mayor parte del PNJCR se encuentra cubierto por ecosistemas de Pino y mixtos (Pino - latifoliado), los cuales se desarrollan desde áreas altas de los cimas de la Cordillera Central como el Pico Duarte y la Rucilla hasta las áreas más bajas en las zonas limítrofes del PNJCR. La variación de la fisonomía de estos bosques refleja su historia. El bosque de pino maduro poco o nada alterado presenta un aspecto homogéneo con árboles de copa redonda y fustes rectos, casi de igual tamaño, densamente distribuidos con una buena cobertura. En el estrato arbustivo de composición variable son frecuentes el tamarindo de loma (Weimannnia pinnata), el Palo blanco (Ilex tuerckheimii), el palo blanco (Garrya fadyenii), el Curamague (Baccaris myrsinites), y el Palo reina (Lyonia heptamera)**.** Sobre los suelos más húmedos son frecuentes las fucsias (Fuchsia triphyla y Fuchsia Pringsheimii). (SEMARN , 2005)

En el estrato arbustivo de composición variable son frecuentes el tamarindo de loma, Weimannia pinnata, el palo blanco (Ilex tuerchkheimii, Mirica picardae), el palo de berraco (Garrya fadyenii), el curamaguey (Baccaris myrsinites, y el palo de reina (Lyonia heptamera). Existen además comunidades vegetales predominantes de la especie de “sabina” Juniperus spp. Sobre los suelos más húmedos son frecuentes las Fucsias, Fuchsia tripbyla y Fuchsia pringsbeimii. El estrato herbáceo se caracteriza por la presencia de los helechos como Pteridium aquilinum, Pteridium angustifolium y Polypodium Lopbosoria quadripinnata. Entre las hierbas es frecuente Siphocampylus rotundifolia. En las zonas más elevadas del parque se desarrolla un pinar abierto constituido por árboles de Pinus occidentalis. Estos pinares abiertos se caracterizan por la presencia de pajón (Danthonia dominguensis) junto a un estrato arbustivo compuesto de arbustos de Baccaris myrsinites y Lyonia spp, los helechos Pteridium aquilinum y Lophosoria quadripinnata. (SEMARN , 2005).

[32] https://jmarcano.com/ecohis/areas/categoria2/ramirez.html

Fauna

El PNJCR, al coincidir con el piso montañoso más alto del país, presenta características únicas en cuanto a la naturaleza del biotopo y la composición de su fauna. Proporciona una amplia gama de hábitats diversos y de biodiversidad. La fauna silvestre contiene un elevado nivel de endemismo. En época que alcanza al pleistoceno y holoceno temprano - al ser los territorios de la Cordillera Central los más antiguos - han servido como centro de radiación de las especies, hacia los nuevos territorios de origen posterior. Entre las especies nativas del grupo de mamíferos en el PNJCR destacan 17 especies de murciélagos, un roedor, la Jutia endémica (*Plagiodontia aedium)* y un insectívoro, el Solenodonte endémico (*Solenodon paradoxus)* los cuales representan una muestra significativa de la fauna total de la isla. Entre las especies introducidas, abundan los jabalíes o puercos cimarrones *(Sus scropha)*, pieza muy apreciada por los cazadores furtivos. Se encuentran los hurones (*Herpestes aeropunctatus)* y poblaciones reducidas de animales domésticos (perros, gatos y ganado mular) en estado cimarrón. Las clases de los anfibios y reptiles son las de mayor representación, entre las cuales se pueden encontrar una serie de lagartijas. Existen también varias especies de serpientes. (SEMARN , 2005).

La avifauna es la clase de mayor abundancia. Entre las más reconocidas podemos encontrar, la Cotorra *(Amazona ventralis)*, el Cuervo *(Corvus leucognaphalus)*, Perico *(Aratinga chloroptera)*, el Canario *(Carduelos dominicensis)*, el Pato chirri *(Calyptophilus frugivorus neibae)*, la Ciguita Julina *(Vireo nanas),* el Zorzal de la selle (*Tordus swalesi)*, la Ciguita del pinar *(Dendroica pinus)* y su subespecies dominicana *Dendroica pinus crysoleuca* restringida a los pinares de la Cordillera Central y Sierra de Bahoruco. Durante los meses invernales se registra el tránsito de múltiples especies migratorias. En total se ha inventariada 80 especies de aves, por un total de 104 especies reportadas para la región de la Cordillera Central. Sin embargo, hasta la fecha no se han efectuado estudios exhaustivos (UASD, EB, 2000, cit. SEMARN , 2005)).

Nombre común	Nombre científico	Nivel de amenaza*
Jutia	*Plagiodontia aedium*	En Peligro de Extinción(EN)
Solenodonte	*Solenodon paradoxus*	En Peligro de Extinción(EN)
Cotorra	*Amazona ventralis*	En Peligro de Extinción(EN)

Tabla 10. Especies Amenazadas del Parque Nacional José del Carmen Ramírez. (SEMARN, 2005)

Amenazas a la Biodiversidad

Las principales amenazas que enfrenta el lugar son el avance de la frontera agrícola y ganadera, la extracción de madera a pequeña escala (de subsistencia), las especies introducidas y/o invasoras .Los incendios forestales provocados generan pérdida de flora y fauna del lugar. También se menciona una grave erosión y presencia de desechos sólidos en los senderos de caminatas. Otra amenaza inminente son las propuestas de desarrollo de infraestructura para producción de energía hidroeléctrica (represas o embalses), (Perdomo *et al*., 2010).

Bibliografía

- SEMARN (2005): Secretaría de Estado de Medio Ambiente y Recursos Naturales. Plan de Manejo del Parque Nacional José del Carmen Ramírez 2005-2009. Santo Domingo, República Dominicana. Abril 2005. http://www.ilustrados.com/tema/9409/Plan-manejo-Parque-Nacional-Jose-Carmen.html
- Perdomo, L., Y. Arias, Y. Léon y D. Wege. (2010). Áreas Importantes para la Conservación de las Aves en la República Dominicana. Parque Nacional José del Carmen Ramírez. Grupo Jaragua y el Programa IBA-Caribe de BirdLife International: República Dominicana. Santo Domingo, República Dominicana.

PARQUE NACIONAL MANGLARES DE ESTERO BALSA

Creación: Fue Creado mediante la Ley 202-04

Administración: Ministerio de Medio Ambiente y Recursos Naturales

Categoría: Parque Nacional

Ubicación: El Parque Nacional Manglares de Estero Balsa está localizado en la Provincia de Montecristi, en la región noroeste de la República Dominicana. Ocupa una superficie total de 56.54 km^2. El límite del área protegida está comprendido entre las siguientes coordenadas UTM en la zona 19Q: Norte 2196046 M, Sur 2178350 M, Este 2196646 M, Oeste 208774 M. El principal centro urbano con incidencia en el Parque es el Municipio Pepillo Salcedo-Manzanillo. [33]

Figura 16. Ubicación del Parque Nacional Manglares de Estero Balsa.[34]

Topografía, hidrología, clima y paisajes

Este parque y su litoral se extiende desde la desembocadura del río Yaque del Norte (es el río más largo del país con 396kms de longitud) hasta el municipio de Pepillo Salcedo. Junto al manglar, los caños y cuerpos de agua del Parque componen hábitat importante para peces, aves y otras especies. Asimismo, forman parte de los atractivos naturales de la zona.

El clima está considerado como semiárido, con una temperatura promedio anual de 27.0 ºC y una precipitación promedio anual de 796 mm. Como ambiente típico de marisma o ciénaga, toda el área del Parque presenta un relieve de pequeña depresión con pendientes entre 0 -4 %. En términos geológicos, el 73.00% del área del Parque corresponde a suelos de marisma o ciénaga costera y el 19.67% constituyen material indiferenciado. El relieve principal allí es una depresión que produce un terreno bajo y pantanoso que se inunda por efecto de la marea y la llegada de las aguas de los ríos y arroyos que desembocan en sus proximidades. La poca elevación del terreno del Parque se presenta en pequeñas dunas y playas que se encuentra allí. Conforme el sistema de clasificación bioclimático de Holdrige, toda el área del Parque corresponde a Bosque Seco Subtropical. En el área del Parque Nacional Manglares de Estero Balsa se pueden diferenciar seis (6) ecosistemas naturales. Estos son: i) Playas, ii) manglares, iii) cuerpo de agua, iv) praderas marinas, v) salados/saladares/salitrales, vi) bosque y matorral seco.

Uso/cobertura	Hectáreas	%
Bosque y matorral seco	662.10	11.64
Cuerpo de agua y saladares	1,443.66	25.39
Manglar	3,420.86	60.16
Salinas	31.22	0.55
Zona urbana y suelo desnudo	96.80	1.70

[33] https://econo-notas1.blogspot.com/2014/12/los-manglares-de-estero-balsa-en.html

[34] http://ambiente.gob.do/wp-content/uploads/2016/10/Parque-Nacional-Manglares-de-Estero Balsa.pdf

Total	**5,685.86**	**100.00**

Tabla 11. Uso y cobertura del Parque Nacional Manglares de Estero Balsa

Figura 17. Bosque de manglar y esteros del Parque Nacional Manglares de Estero Balsa.[35]

Flora

Se reportan para el área del Parque 201 especies de plantas vasculares, pertenecientes a 87 familias. Once (11) especies son endémicas de la Isla Hispaniola. 178 son nativas, nueve (9) introducidas y una (1) naturalizada (Ministerio Ambiente, 2014). Un total de 16 especies amenazadas se reportan para el Parque (Tab. II). Las especies invasoras presentes allí son Leucaena o Lino *(Leucaena leucocephala)* y Acacia amarilla (*Senna siamea).* (Ministerio de Medio Ambiente y Recursos Naturales, 2011),(MMARN (2015).

NOMBRE CIENTIFICO	NOMBRE COMUN	ESTATUS	CATEGORIA DE AMENAZA y CITES
Roystonea hispaniolana	Palma real	Endémica	VU
Conocarpus erectus	Mangle de botón	Nativa	VU
Sabal domingensis	Palma cana	Endémica	EP
Tillandsia usneoides	Guajaca	Nativa	VU
Vanilla dilloniana	Vanilla	Nativa	EP
Broughtonia domingensis	Flor de mayo	Endémica	EP
Maclura tinctorea	Mora, fustete	Nativa	VU
Leptocereus weingartianus	Cayuco	Endémica	EP
Swietenia mahagoni	Caoba	Nativa	VU, CITES
Guaiacum officinale	Guayacan	Nativa	PC
Guaiacum sanctum	Vera	Nativa	VU
Oeceoclades maculata	Orquídea africana	Naturalizada	CITES
Avicennia germinans	Mangle prieto	Nativa	EP
Ceiba pentandra	Ceiba	Nativa	EP
Rhizophora mangle	Mangle rojo	nativa	EP
Laguncularia racemosa.	Mangle blanco	Nativa	VU

Tabla 12. Especies de plantas amenazadas reportadas para el parque. MMARN (2015).
Nota: VU=Vulnerable, EP= En Peligro, PC= Peligro Crítico. CITES = Convenio CITES.

Fauna

Se reporta un total de 89 especies de fauna para el Parque, distribuidas de la siguiente manera: i) cuatro (4) especies de crustáceos, ii) 15 especies de peces de importancia comercial, iii) tres (3) especies de anfibios, iv) 18 de reptiles, v) 49 especies de aves. (MMARN (2015), que se describen a continuacion:

[35] https://venamontecristi.com/?ruta=ruta-parque-nacional-subacuatico

Crustáceos: En el interior del manglar es común encontrar algunas especies de crustáceos como, Cangrejo de coco *(Cardisoma guanhumi)*, Cangrejo de manglar *(Ucides cordatus)*, Jaiba cirica (*Callinectes sapidus) y Gecarcinus ruricola*.

Anfibios*:* Estudios recientes de mayo 2014 reportan tres (3) especies de anfibios para la zona del Parque, de las cuales dos (2) son introducidas y una endémica. Las dos especies introducidas son el maco pempem (*Rhinella marina = Bufo marinus*) y la rana toro (*Lithobates catesbianus*= *Rana catesbeiana*). La especie endémica es *Osteopilus dominicensis*.

Reptiles: Se reportan 18 especies de reptiles para la zona del Parque. Las mismas, corresponden a la clase Reptilia, ordenes Squamata y Testudines, y a las familias Dactyloidae, Gekkonidae, Iguanidae, Leiocephalidae, Sphaerodactylidae, Teiidae, Boidae, Dipsadidae, Cheloniidae y Emydidae (anexo 1). De las 18 especies, tres (3) son nativas de la Isla Hispaniola, dos (2) introducidas y 13 son endémicas de la isla, equivalentes al 12% de las 105 especies conocidas para la República Dominicana. Casi todas las especies presentes allí son de amplia distribución a nivel de la Hispaniola. Las especies observadas con más frecuencia fueron: Leiocefalo con máscara de La Hispaniola (*Leiocephalus personatus*), Ameiva gigante de La Hispaniola (*Ameiva chrysolaema*) y Anolis grácil de La Hispaniola (*Anolis distichus)*. Entre las especies reportadas figura la tortuga carey (*Eretmochelys imbricata*), especie considerada en Peligro Critico a nivel global. La zona del Parque es considerada sitio de alimentación y refugio para juveniles de esta especie.

Aves: En el area se mencionana un total de 49 especies de aves, pertenecientes a 27 familias. Del total de especies, 35 son residentes (3 de ellas con población migratoria), cinco (5) son endémicas, siete (7) migratorias, una (1) introducidas y una (1) colonizadora**.** Las especies endémicas observadas son: Cigua palmera (*Dulus dominicus*), Pájaro bobo (*Coccyzus longirostris = Saurothera longirostris*), Carpintero (*Melanerpes striatus*), Cuatro ojos (*Phaenicophilus palmarum*) y Barrancolí (*Todus subullatus*). En relación a especies amenazadas, se observaron el Flamenco (*Phoenicopterus ruber*), la Garza rojiza (*Egretta rufecens*), la Cuchareta (*Platalea ajaja*) y la Cigüita de manglar (*Setophaga petechia = Dendroica petechia*). Todas estas especies figuran como "Vulnerables" en la Lista Nacional de Especies Amenazadas (Ministerio Ambiente, 2011). Especies de aves presentes en el Parque y que figuran en el Apéndice II de la Convención CITES, son: el Zumbadorcito (*Mellisuga mínima*), Zumbador grande (*Anthracothorax dominicus*) y el Guaraguao (*Buteo jamaicensis*).

Mamíferos marinos**:** En la zona marina del Parque se reportó en el 2010 el varamiento de un ballenato de Ballena jorobada (Megaptera novaeangliae), que fue rescatado por técnicos del Ministerio de Medio Ambiente. Las ballenas jorobadas nadan por la zona cercana a la bahía de Manzanillo, Cayos Siete Hermanos y el Parque Nacional Submarino Montecristi.

Amenazas a la Biodiversidad

Sobrepesca y pesca con artes de pesca reguladas o prohibidas. Incursión de pescadores haitianos y conflictos con pescadores dominicanos. Cacería y captura de especies. Ganadería extensiva (chivos y ovejos) en alrededores del Parque. Contaminación de cursos de agua y residuos sólidos que llegan a los manglares. Ubicación de vertedero municipal en Montecristi. Derrame de combustibles y otras sustancias contaminantes producto de la operación del Puerto de Manzanillo. Presión por desarrollo de urbanizaciones en la zona. Desconocimiento por parte de la población local acera de la importancia del Parque y sus recursos. Deficiencia en la gestión del Parque: personal, logística, equipos, ejecución, evaluación y monitoreo. MMARN (2015).

Bibliografía

- MMARN (2015). Ministerio de Medio Ambiente y Recursos Naturales.: Plan de manejo parque nacional manglares estero balsa: 2015-2020.Santo Domingo, República Dominicana. Febrero 2015. http://caribbean-rris.biopama.org/sites/default/files/2020-03/Plan%20 de%20Manejo %20 PN%20Manglares%20Estero%20Balsa.pdf
- Ministerio de Medio Ambiente y Recursos Naturales. 2011. Lista de especies en peligro de extinción, amenazadas o protegidas de la Republica Dominicana: Lista Roja. Santo Domingo, República Dominicana. 41 p.

PARQUE NACIONAL NALGA DE MACO

Creación: Este Parque Nacional fue creado mediante el Decreto Presidencial No. 221-95.

Administración: Ministerio de Medio Ambiente y Recursos Naturales

Categoría: Parque Nacional

Ubicación: Loma Nalga de Maco (LNM) está localizada en el extremo occidental de la Cordillera Central, cerca de la frontera con Haití. Gran parte se encuentra en el municipio de Río Limpio (Provincia Elías Piña), pero al norte también ocupa parte del municipio de San Ignacio de Sabaneta (Provincia Santiago Rodríguez). Posee un territorio de 278 km², aproximadamente. La montaña Nalga de Maco, con 1,990 metros de altitud, caracteriza este parque; es la montaña más alta de la Cordillera Central occidental.

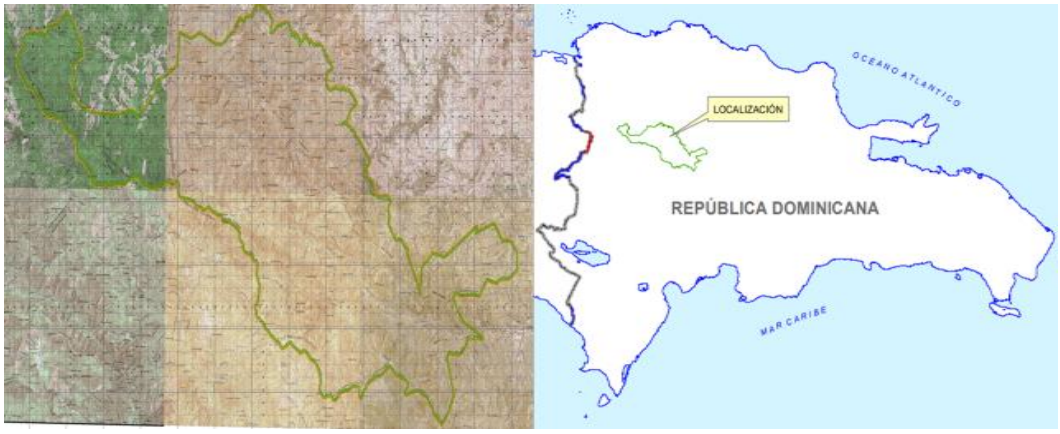

Figura 18. Ubicación del Parque Nacional Nalga de Maco.[36]

Topografía, hidrología, clima y paisajes

Nalga de Maco es una montaña de gran riqueza hidrográfica. En su área de influencia nacen los ríos Artibonito, Joca, La Cidra y El Valle. El río Artibonito es el mayor sistema fluvial de la isla de Santo Domingo. A lo largo de su recorrido por esta bella serranía el río circula bastante encajonado atravesando cañones y desfiladeros de gran belleza. El clima predominante es tropical templado húmedo de altura con lluvias abundantes durante casi todo el año y temperaturas que fluctúan entre los 11 y los 16ºC. La temperatura suele ser bastante fría durante la noche en la cima y fuertes vientos pueden soplar durante varios días.

La montaña Nalga de Maco es la montaña más alta de la Cordillera Central occidental, próximo a la frontera con Haití. En la cima de Nalga de Maco se encuentra el único "bosque enano" localizado en la isla. La existencia de dicho bosque se debe a la presencia permanente de vientos. El relieve es muy accidentado, con áreas geográficas y depresiones de difícil acceso. La altitud varía desde los 650 msnm en la parte más baja a los 2000 metros de altitud. La cima de Nalga de Maco se encuentra generalmente rodeada de nubes cargadas de humedad y neblina, que favorecen un extenso bosque nublado compuesto de troncos torcidos, ramificación profusa y una gran cantidad de epífitas (musgos y orquídeas) que pueden cubrir completamente las ramas de los árboles y la superficie del esponjoso suelo. En general, la vegetación es siempre verde, con árboles de copas grandes, de forma regular y hojas anchas.

Flora

La composición florística es rica y presenta un alto endemismo, muy acentuado en la vegetación de la cima. Se encuentra presente además, un bosque enano, único en el país. Entre las especies de más importancia para la conservación, destacan *Podocarpus hispaniolensis* (EN), la Palma manacla (*Prestoea montana*) y los helechos

[36] http://ambiente.gob.do/wp-content/uploads/2016/10/Parque-Nacional-Nalga-de-Maco-1.pdf

arborescentes (*Cyathea* sp). La vegetación de la LNM está compuesta por varias comunidades, algunos de estas, poco alteradas, excepto en las partes más bajas, donde se encuentran cultivos (temporales y permanentes). En general, la vegetación es siempre verde. El estudio de SEA/DVS (1992b, cit. Perdomo et al, 2010) sugiere la siguiente clasificación: Bosques Latifoliados siempre verdes y Zonas de Cultivos.

Figura 19. Montaña Nalga de Maco en la Cordillera Central. Se observa rodeada de nubes cargadas de humedad.[37]

Como ejemplo de estas formaciones vegetales se destacan (Perdomo et al, 2010): Bosques de sombra (bosque de *Sloanea ilicifolia* y Manaclares de cuenca de *Prestoea montana*); Bosques nublados (bosque de Palo de viento -*Didymopanax tremulus*-), Bosque abierto sobre rocas con Palo de burro (*Dendropanax arboreus*), *Coccothrinax* sp., especies epífitas, lianas y arbustos, y bosque enano de *Coccoloba pauciflora* y *Podocarpus hispaniolensis*; Bosques ribereños del Río Vallecito con Palo de cotorra (*Casearia sylvestris*), Yagrumo (*Cecropia peltata*) y Hoja ancha (*Cordia sulcata*), entre otras. Tres de sus especies emblemáticas, están en peligro: Palma manacla (*Prestoea montana*), Helecho arborescente (*Cyathea* sp) y Podocarpus hispaniolensis.

Fauna

De acuerdo a las listas del Programa IBA de República Dominicana, en Loma Nalga de Maco se han reportado 79 especies de aves. Esto incluye reportes de Cúa (Coccyzus rufigularis) en la zona Río Limpio-Carrizal (Latta et al., 2006 cit. Perdomo et al, 2010). Esta rara especie es considerada en Peligro de extinción, según la Unión Mundial para la Naturaleza (UICN). También se han identificado 7 especies de anfibios endémicos amenazados, a saber: la Rana de los arroyos del norte (*Eleutherodactylus schimidti*, CR), la Rana martillo del norte (*E. auriculatoides*, EN), la Rana de las montañas de la Hispaniola (*E. montanus*, EN), la Rana arborícola de La Española (*Osteopilus pulchrilineatus*, EN), la Rana telégrafo de La Española (*E. audanti*, VU), la Rana silbadora de Haití (*E. wetmorei*, VU), y la Rana arborícola verde de La Española (*Hypsiboas heilprini*, VU). El mayor número de anfibios se presenta en la zona de Rio Limpio, donde predomina una vegetación ribereña mezclada con zonas de cultivo, (Perdomo et al. 2010).

Amenazas a la Biodiversidad

Las principales amenazas mencionadas son: agricultura, especialmente con prácticas de tumba y quema, extracción de madera, ganadería, incendios forestales, fenómenos naturales. Otras amenazas más recientes son la invasión de terrenos, asentamientos humanos y prácticas inapropiadas de uso y manejo de la tierra producto de movimientos migratorios provenientes de la República de Haití, (Perdomo et al. 2010).

Bibliografía

- Perdomo, L., Y. Arias, Y. León y D. Wege. (2010). Áreas Importantes para la Conservación de las Aves en la República Dominicana. Parque Nacional Nalga de Maco-Rio Limpio. Grupo Jaragua y el Programa IBA-Caribe de BirdLife International: República Dominicana. http://www.grupojaragua.org.do/documents/AICAS/DR-IBAS_2010_DO002 _Loma_Nalga_ de_

[37] https://www.pinterest.com/pin/546554104754342189/

Maco-Rio_Limpio.pdf

PARQUE NACIONAL PICKY LORA

Creación: Fue creado mediante los Decretos Presidenciales 571-09 y 249-11

Administración: Ministerio de Medio Ambiente y Recursos Naturales

Categoría: Parque Nacional

Ubicación: El Parque Nacional Picky se encuentra localizado en el municipio de Monción, Santiago Rodríguez, tiene una superficie de 112.28 kilómetros cuadrados, y en él nacen los ríos Amina, Mao y el arroyo Agua Hedionda. El mismo fue incorporado al Sistema Nacional de Áreas Protegidas (SINAP) mediante el Decreto No.571-09 de fecha 07 de agosto, 2009 como Parque Nacional Amina; sin embargo el Decreto No. 249-11 se le da el nombre de Parque Nacional Piky Lora. El Municipio de Monción en el cual se localiza el Parque Nacional Piky Lora pertenece a la Provincia de Santiago Rodríguez. El Parque está ubicado en las estribaciones de la Cordillera Central, frente al monte Gallo; limitado al norte con la provincia de Valverde Mao, al sur y al este con San José de las Matas y al oeste con el municipio de San Ignacio de Sabaneta.

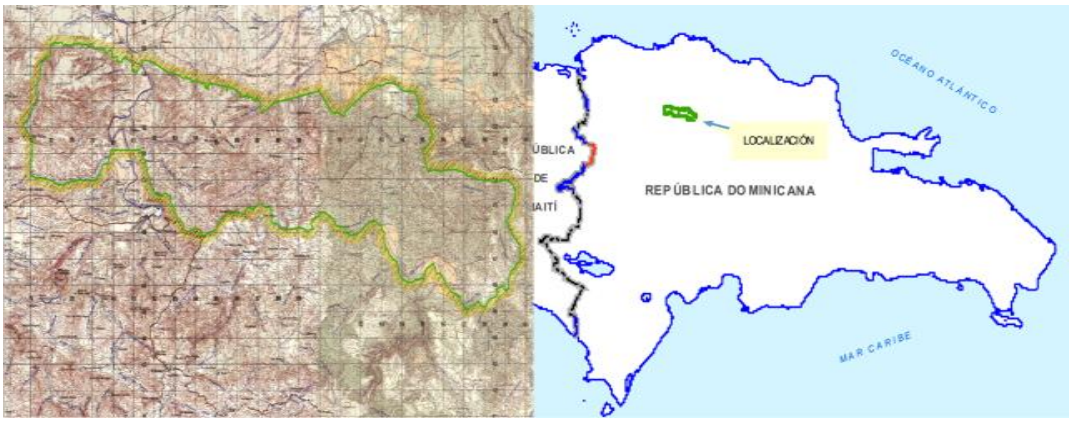

Figura 20. Ubicación del Parque Nacional Picky Lora. [38]

Topografía, hidrología, clima y paisajes.

El Parque Nacional Piky Lora abarca pequeñas montañas paralelas al valle del Cibao Occidental, al pie de la Cordillera Central, es un área con ambiente particular con cactus, bromelias, orquídeas y otra vegetación típica de la zona. La geología, conjuga dos orígenes, uno, derivado de la intensa actividad volcánica ocurrida en la Cordillera Central, en donde predominan rocas sedimentarias, magnéticas, tonalitas y los granitos del cretácico. De otro lado, formaciones de tipo Gurabo compuesto por aluviones, depósitos marinos, fluviales, abanicos de lajas con arcillas, terrazas cañones y cerros del cuaternario. (Sanó et al, 2013). El relieve varia de plano hasta muy accidentado la pendiente es alrededor de un 50%, los suelos son pedregoso, aluvionales y arcilloso. Precipitaciones media anual variando de 600 mm a 800 mm/año y temperatura media anual de 24.2 grados centígrado.

[38] http://ambiente.gob.do/wp-content/uploads/2016/10/Parque-Nacional-Picky-Lora.pdf



Figura 21. Parque Nacional Piky Lora.[39]

En general se identifican cinco zonas bien diferenciadas: Bosques Secos, Bosques de transición, Bosques ribereños, Bosque mixto con algunos pinos y Humedal de agua dulce.

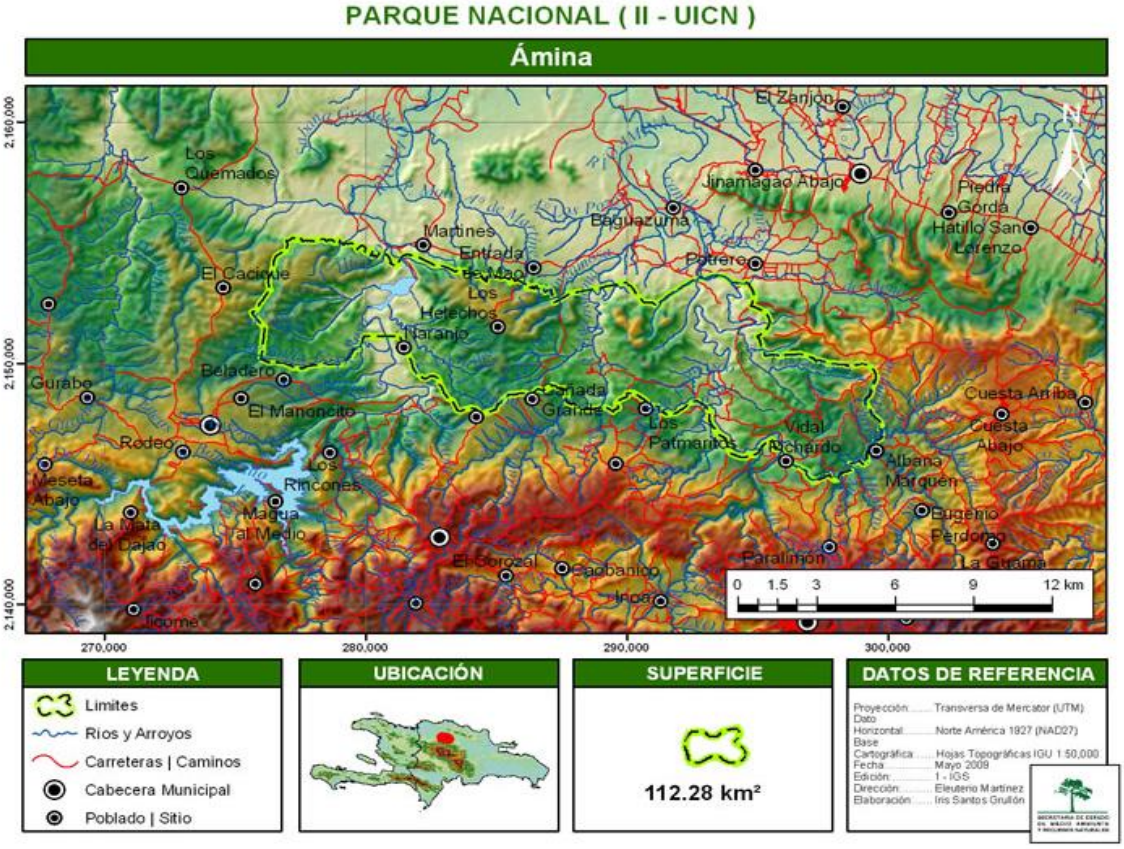

Figura 22. Ubicación, relieve y entorno del Parque Nacional Piky Lora (antes conocido como Amina)[40]

Flora

En el área del Parque se mencionan 314 especies de plantas vasculares, de las cuales 58 son endémicas, 244 nativas de la isla La Española, una (1) naturalizada, 11 introducidas, distribuidas en 247 géneros, 92 familias de plantas. También algunas especies Gimnosperma como el caso del *Pinus occidentalis.* Es importante señalar que, el endemismo de esta área es bastante alto, el cual representa aproximadamente el 19 % del total de las especies observadas. De las 92 familias identificadas, las que presentan mayor número de especies son: Morácea, Myrtaceae Verbenáceae, Urticácea, Fabaceae, Euphorbiaceae, Malvacea,Poaceae, Asterácea, Borraginaceae, Mimosácea. Los géneros más abundantes son: Coccothrinax, Sabal, Pseudophoenix, Bursera, Canela, Tetragastris, Guaiacun, Trichilia, Eugenia y Agave. De acuerdo a su forma de vida, tipo biológico o hábito de crecimiento, el total de las especies reportadas para el área de estudio se distribuye de la siguiente

[39] https://www.accionverde.com/parque-nacional-amina/
[40] Idem

manera: 75 son hierbas o herbáceas 127 arborescentes, 77 arbustivas, 26 lianas o bejucos, una (1) rastrera y dos (2) estípites o palmas. (Sanó et al, 2013).

NOMBRE CIENTIFICO	NOMBRE COMUN	ESTATUS	CATEGORIA DE AMENAZA
Tabebuia obovata	Aceituno	Endémica	EP
Roystonea hispaniolana	Palma real	Endémica	VU
Zombia antillarum	Guanillo	Endémica	PC
Caesalpinia pellucida	Endémica	PC	---
Sabal domingensis	Palma cana	Endémica	CR
Swietenia mahagoni	Caoba	Nativa	EP, CITES
Canella winterana	Canela de tierra	Nativa	VU
Consolea monilifornis	Alpargata	Nativa	VU
Melocactus lemairei	Melón espinoso	Endémica	VU, CITES
Leptocereus weingartianus	Cayuco	Endémica	EN
Pilosocereus polygonus	*Cayuco*	Endémica	VU
Amyris elemifera	Guaconejo	Nativa	VU
Maclura tinctorea	Mora	Nativa	EN
Cyrtopodium punctatum	Cañuela	Nativa	EN
Opuntia antillrum	Tuna	Nativa	VU
Coccoloba leoganensis	Uva cimarrona	Endémica	Rara
Pseudophoenix vinífera	Cacheo	Endémica	PC
Picrodendron baccatum	Ahoga vaca	Nativa	Rara
Coccothrinax fragrans	Guanito	Nativa	PC
Cedrela odorata	Cedro	Nativa	PC
Jacaranda poitaei	Abey	Endémica	PC
Caesalpinia barhonensis	Palo de Brasil	Endémica	PC
Copernicia berteroana	Yarey	Endémica	---
Simarouba berteroana	Aceituno	Endémica	EN
Pinus occidentalis	Pinus cuaba	Endémica	PC
Oeseoclades maculata	Orquídea africana	Naturalizada	CITES
Eugenia odorata	Escobon	Endémica	VU
Agave antillarum	Maguey de bestia	Endémica	EN
Mammillaria prolifera	Bombillito	Nativa	VU, CITES
Dendrocereus undatus	Cayuco	Nativa	CR
Guaiacum officinale	Guayacán	Nativa	VU, CITES
Vanilla sp.	Vainilla	Nativa	EN, CITES
Tillandsia usneoides	Guajaca	Nativa	VU
Tillandsia setaceae	Bromelia	Nativa	VU
Harrisia sp.	Yasa	Endémica	EN,CITES

Tabla 13. Lista de plantas amenazadas (Sanó et al, 2013).

Fauna

Mamíferos: En la Presa de Mención dentro del Parque Nacional Piky Lora, se ha observado la presencia del Murciélago pescador (Noctilio leporinus) de la familia Noctilionidae (Garcia Marcano, comunicación personal, 2013, cit. Sanó et al, 2013), dicho múrcialo es común en la referida presa. Otros mamíferos reportados para el área protegida son el Solenodonte (Solenodon paradoxus) y la Jutia (Plagiodontia aediun), ambas especies están incluidas en Peligro de Extinción (EP) en la Lista Roja de Animales Silvestres Amenazados en la República Dominicana. (Sanó et al, 2013).

Anfibios y reptiles amenazados:

Grupo/Especie	Fuentes	
Anfibios	UICN	MA
Hypsiboas heilprini	VU	VU
Osteopilus pulchrilineatus	EN	EP
Osteopilus vastus	EN	EP
Reptiles		
Trachemys stejnegeri	VU	
Totales de especies 4	3	4

Tabla 14. Anfibios y reptiles amenazados, Parque Nacional Piky Lora (Sanó et al, 2013).

Leyenda: UICN (2012); VU= Vulnerable; CR= En Peligro crítico; EN= En Peligro; MA=Ministerio Ambiente (2011); EP= En Peligro; PC= Peligro crítico (según Lista Roja, dominicana)

***Avifauna*:** En el Parque Nacional Piky Lora, se han observado 60 especies de aves, de las cuales 36 son residentes, dos (2) de ellas con poblaciones migratorias, nueve (9) endémicas, una (1) colonizadora, dos (2) introducidas y 12 especies migratorias. Las especies endémicas(9 en total) observadas en el parque son: El carpintero (*Melanerpes striatus*), Cigua palmera (*Dulus dominicus*), nuestra Ave Nacional, el Cuatro ojos (*Phaenicophilus palmarum*), Pájaro bobo (*Coccyzus longirostris*), Carpinterito de sierra (*Nesoctites micromegas*), el Pitanguá (*Caprimulgus cubanensis*), el que ha sido reportado por el administrador del parque por la loma de Las Auyamas (Vertiente Oeste); la Ciagua canaria (*Icterus dominicensis*), el Barrancolí (*Todus subullatus*) y Chi-cui (*Todus angustirrostris*). (Sanó et al, 2013).

Nombre común	**Nombre científico**	**Nivel de amenaza***
Flamenco	Phoenicopterus ruber	Vulnerable
Cigua canaria	Icterus dominicensis	Vulnerable
Yaguasa	Dendrocygna arbórea	Peligro de Extinción

Tabla 15. Aves amenazadas en al Parque Nacional Piky Lora

En relación a aves incluidas en la Convención que regula el Comercio de Especies Amenazadas de Fauna y Flora Silvestres (CITES, 2011, cit. Sanó et al., 2013) están: el Zumbadorcito (*Mellisuga mínima*), Zumbador grande *Anthracothorax dominicus*), la Cuyaya (*Falco sparverius*) y el Guaraguao (*Buteo jamaicensis*).

Se han registrado además, 12 especies migratorias. Dentro de ellas: La Cigüita parula (*Parula americana*), Bijirita (*Setophaga ruticilla*), Cigüita tigrina (*Setophaga tigrina = Dendroica tigrina*), Cigüita de los prados, (*Setophaga discolor = Dendroica discolor*), Cigüita saltarina (*Seiurus aurocapillus*), Cigüita del agua (*Parkesia noveboracensis = Seiurus noveboracensis*), Cigüita enmascarada (*Geothlypis trichas*) y el Pega palo (Mniotilta varia). También se incluyen tres (3) Patos, de la Florida (*Anas discors*), Pato turco (*Aythya affinis*) y Pato negro (*Aythya collaris*), por último el Guincho (*Pandion haliaetus*). Es de suma importancia resaltar el hecho de que en el Parque Nacional Piky Lora se han registrado varios casos de posible albinismo producto de mutaciones

en algunas especies de aves como son: La Cuyaya (*Falco sparverius*) Rolita (*Columbina passerina*) y el Ruiseñor (*Mimus polyglottos*), estas últimas han sido observadas por moradores de las comunidades del referido parque. (Sanó et al., 2013)

Amenazas a la Biodiversidad: degradación de los ecosistemas por la actividad antropogénica.

Bibliografía consultada:

- Rolando Sanó, Darío Flores Chávez, Christopher Esquea, Ignacio Fernández y Domingo Sirí Núñez (2013) INFORME EVALUACION SOBRE LA BIODIVERSIDAD DEL PARQUE NACIONAL PIKY LORA, MONCION, PROVINCIA SANTIAGO RODRIGUEZ. Viceministerio de Áreas Protegidas y Biodiversidad

MONUMENTO NATURAL DIEGO DE OCAMPO

Creación: Ley 202-04 Sobre Áreas Protegidas

Administración: Ministerio de Medio Ambiente y Recursos Naturales

Categoría: Monumento Natural

Ubicación: El área protegida Diego de Ocampo está dentro de la categoría III que corresponde a Monumento Natural, del Sistema Nacional de Área Protegida .Está localizada Geográficamente dentro de las coordenadas 19°36'8.012"N y 19°33'36.451"N latitud norte y 70°49'21.023"W y 70°43'43.548"W longitud oeste. Tiene una superficie total de 25.34 km², de la cual el 93.65 % (23.74 km²) está dentro de territorio de la provincia Santiago, que incluye la Sección de Palmar Arriba, perteneciente al D.M., que lleva el mismo nombre, la Sección Ranchito del municipio cabecera de Santiago, Las secciones Las Lavas, Macorís del Limón y Palmar Abajo perteneciente al municipio Villa González y en la provincia Puerto Plata, la sección Escalera del municipio de Altamira.

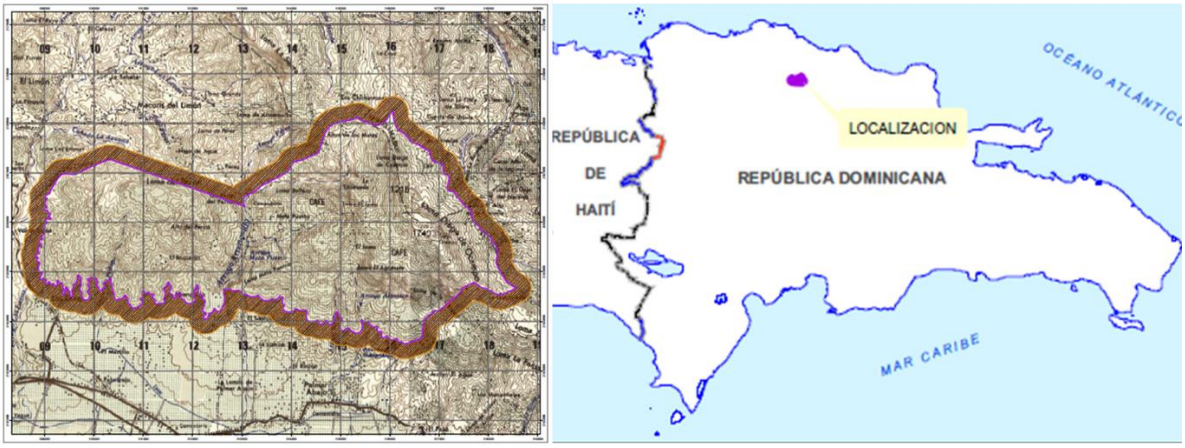

Figura 26. Ubicación del Monumento Natural Diego de Ocampo.[41]

[41] http://ambiente.gob.do/wp-content/uploads/2016/10/Monumento-Natural-Pico-Diego-de Ocampo.pdf

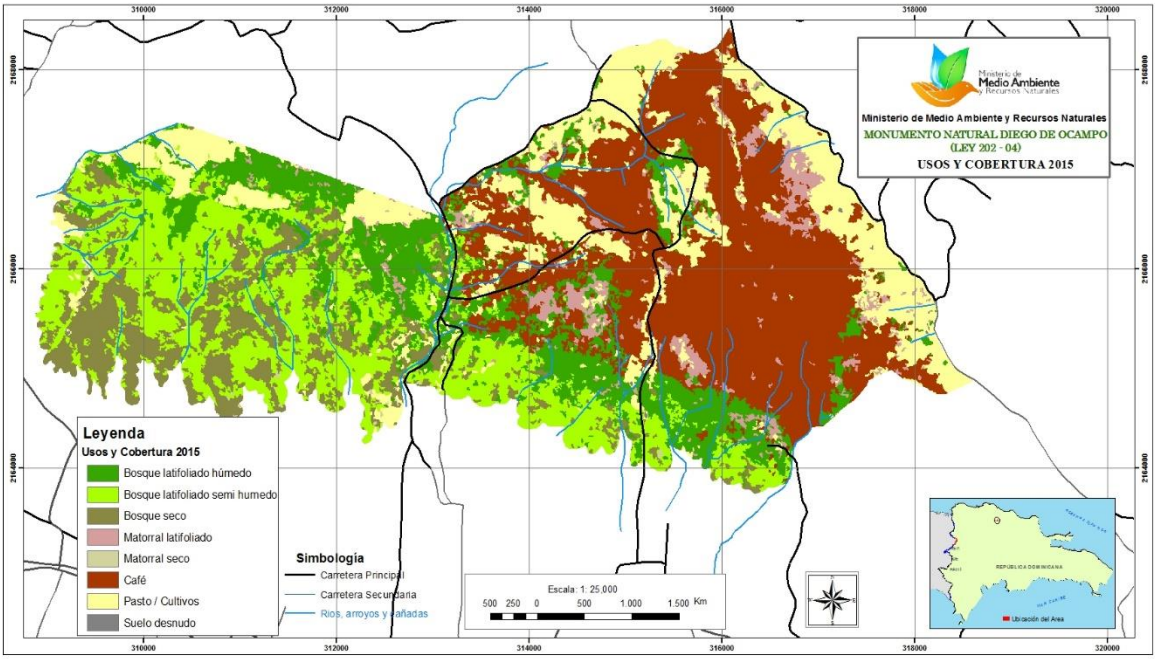

Figura 27. Uso y cobertura del suelo en el Monumento Natural Diego de Ocampo.

Topografía, hidrología, clima y paisajes

El monumento natural Diego de Ocampo, se considera una zona de recarga de agua y las principales fuentes hídricas nacen por encima de los 700 msnm, incluidas las lomas Diego de Ocampo, con 1230 msnm, El Jamo con 900 msnm, Loma El Peñón con 775 msnm y Alto de Los Mates con 951 msnm. Los patrones de lluvia de la Loma Diego de Ocampo pueden ser parecidos al promedio anual de lluvia para el Valle del Cibao (Santiago), que es de 980,5 mm/anual. La temperatura promedio varía de 21° C (en diciembre) hasta 28° C (en agosto). (Viceministerio de Áreas Protegidas y Biodiversidad. 2018). La montaña Diego de Ocampo está formada por rocas calizas, algunas cristalizadas y otras muy meteorizadas, con muchas fragmentaciones producidas por los movimientos telúricos que generaron grietas y furnias. También existen algunas cavernas propias de este tipo de formación geológica.

Figura 28. Montaña Diego de Ocampo en la Cordillera Central formada en gran parte por bosque latifoliado.[42]

Flora

Se han observado aproximadamente 414 especies de plantas vasculares de las cuales 27 son Endémicas, 334 Nativas de la isla Española, 20 naturalizadas, 32 introducidas, distribuida en, 96 familias de plantas

[42] https://www.accionverde.com/monumento-natural-pico-diego-de-ocampo/

(Viceministerio de Áreas Protegidas y Biodiversidad, 2018). Existe en el área protegida un 6.6 % de endemismo del total de las especies observadas. De las 96 familias identificadas, las que presentan mayor número de especies son: *Morácea, Mirtáceas Verbenaceae, Sapindácea, Fabaceae, Euphorbiaceae, Malvácea, Poaceae, Rutaceae, Borraginácea, Mimosaceae. Los géneros más abundante son: Sabal, Pinus, Bursera, Poitaea, Tetragastris, Trichilia, Eugenias, Terstroemia, Lysiloma, Comocladia, Roystonea.* En el monumento natural se reportan 39 especies amenazadas o protegidas, las cuales, se distribuyen de la siguiente manera: 9 endémicas, 30 nativas, mientras en cuanto a nivel de amenaza, la situación es: 22 Vulnerable (VU), 11 en peligro (EN), 4 en preocupación menor (LC) y 2 (CR).

NOMBRE CIENTIFICO	NOMBRE COMUN	ESTATUS	CATEGORIA DE AMENAZA
Roystonea hispaniolana	Palma real	Endémica	VU
Annona glabra	Bagá, Anón de rio	Nativa	VU
Broughtonia domingensis (Lindl.) Rolf	Flor de mayo	Nativa	VU
Sabal domingensis	Palma cana	Endémica	VU
Swietenia mahagoni	Caoba	Nativa	VU
Gesneria viridiflora	Gesneria	Endémica	LC
Erythroxylum rufum	Papelillo	Nativa	LC
Krugiodendron ferreum (Vahl) Urb	Quiebra hacha	Nativa	VU
Prestoae montana	Manacla	Nativa	VU
Justicia spinosissima Alain	Camarón	Endémica	CR
Mappia racemosa	---	Nativa	CR
Calycogonium domatiatum	---	Endémica	EN
Cyrtopodium punctatum	Cañuela	Nativa	EN
Cedrela odorata	Cedro	Nativa	EN
Prunus myrtyfolia	almendro	Nativa	VU
Pouteria dictyoneura (Griseb.) Radlk.	Caracol	Nativa	VU
Agave antillarum	Maguey	Endémica	VU
Cecropia schreberiana	Yagrumo	Nativa	VU
Chrysophyllum cainito	Caimito	Nativa	EN
Anonna reticulata	Mamón	Nativa	EN
Schefflera morototoni (Aubl	Palo de viento	Endémica	VU
Petitia domingensis	Capa de sabana	Nativa	VU
Byrsomina spicata	Maricao	Nativa	VU
Theophrasta americana L.	Guayaba de indio	Endémica	EN
Cyathea arborea.	Helecho	Nativa	EN
Vanilla dilloniana.	Vainilla	Nativa	EN
Brunellia comocladifolia	Palo de Cotorra	Endémica	LC
Tetragastris balsamifera	Amacey	Nativa	LC
Mammea americana	Mamey	Nativa	EN
Hylocerus undulatus	Pitahaya	Nativa	VU
Amyris elemifera L.	Guaconejo	Nativa	EN
Canella winterana	Canela de tierra	Nativa	VU
Guaiacum officinale L.	Guayacan	Nativa	VU
Guaiacum sanctun L	Vera	Nativa	VU
Tillandsia usneoides	Guajaca	Nativa	VU
Sapindus saponaria L.	Jaboncillo	Nativa	VU

Colubrina arborescens	Corazón de paloma	Nativa	VU
Cordia sulcata	Friega plata	Nativa	VU
Genipa americana	Jagua	Nativa	EN

Tabla 18. Especies de plantas amenazadas del Monumento Natural Diego de Ocampo

Categorías de Amenaza (CE): EP: En Peligro, PC: Peligro Crítico, VU: Vulnerable.

Fauna

Anfibios: Se han reportado 11 especies de anfibios, de las cuales 9 son endémicas y dos (2) introducidas, para un 23% de las 44 especies endémicas de la República Dominicana, cinco (5) se encuentran amenazadas; el sapo crestado sureño (*Peltophryne guentheri*) (CR, PC), rana de los arroyos del Norte (*Eleutherodactylus schmidti*), (CR, PC), la rana arborícola verde de la Hispaniola (*Hypsiboas heilprini*), (VU), rana arborícola amarilla de la Hispaniola (*Osteopilus pulchrilineatus*), (VU, EP) y la rana arborícola gigante de la Hispaniola (*Osteopilus vastus*), (VU, EP), tanto para la Lista Roja (UICN), como para la lista roja de Medio Ambiente, (MA). En lo que se refiere al endemismo, de las nueve (9) especies ocho (8) son endémicas y una (1) introducida, para un 18% de las 44 especies endémicas de la Republica Dominicana. Cabe destacar que el Monumento Natural Pico Diego De Ocampo, tiene un alto endemismo en lo que respeta al grupo de los anfibios (Viceministerio de Áreas Protegidas y Biodiversidad, 2018).

Clase/Orden/Familia Amphibia/Anura	Nombre Científico	Nombre Común	Amenaza UICN	MA
Bufonidae	*Rhinella marina*	Maco pempen		
Eleutherodactylidae	*Eleutherodactylus abbotti*	Calcalí		
Eleutherodactylidae	*Eleutherodactylus flavescens*	Rana amarilla de dedos hendidos	NT	
Eleutherodactylidae	*Eleutherodactylus inoptatus*	Rana gigante de la Hispaniola		
Eleutherodactylidae	*Eleutherodactylus schmidti*	Rana de los arroyos del Norte	CR	PC
Eleutherodactylidae	*Eleutherodactylus weinlandi*	Rana de rabadilla roja de la Hispaniola.	LC	
Hylidae	*Hypsiboas heilprini*	Rana arborícola verde de la Hispaniola.	VU	VU
Hylidae	*Osteopilus dominicensis*	Rana arborícola reidora Hispaniola		
Hylidae	*Osteopilus vastus*	Rana arborícola gigante de la Hispaniola	EN	EP

Tabla 19. Anfibios endémicos del Monumento Natural Diego de Ocampo y grado de amenaza.

Reptiles: En el área se reportan un total de 25 especies de reptiles, de los cuales cuatro (4) se encuentran con algún grado de amenaza: la Lucia gigante de la Hispaniola (Celestus warreni), (EP), Anolis gigante de Dominicana (Anolis baleatus), (EP), la Boa esbelta de la Hispaniola (Chilabothrus gracilis), (EP) y l aJicotea norteña (Trachemys stejnegeri), (VU). El Monumento Natural Pico Diego De Ocampo, posee un alto endemismo en el grupo de los reptiles, con 2 especies Nativas, y 23 endémicas del total de 25 especies identificadas.

Avifauna: Se han descrito 34 especies de aves, pertenecientes a 22 familias. De esas, se han reportado 11 especies endémicas: la Cigua palmera (*Dulus dominicus*), el Ave Nacional, el Cuatro ojos (*Phaenicophilus palmarum*),Pájaro bobo (*Coccyzus longirostris*), Barrancolí (*Todus subulatus*), Carpintero (*Melanerpes striatus*), Carpinterito de sierra (*Nesoctites micromegas*), así como la Cotorra (*Amazona ventralis*), Perico

(*Psittacara chloroptera*), Cuervo (*Corvus leucognaphalus*), Cao (*Corvus palmarum*) y el Papagayo (*Priotelus roseigaster*).

En cuanto a aves amenazadas, se han registrado siete (7) especies: la Perdiz cabeza blanca (*Geotrygon leucometopia*), Cotorra (Amazona ventralis), Perico (Psittacara chloroptera), Ouervo (*Corvus leucognaphalus*), las cuales se encuentran incluidas en la categoría de en Peligro (EN)**;** mientras que la Paloma ceniza (*Patagioenas inornata*), el Papagayo (*Priotelus roseigaster*) y el Cao (*Corvus palmarum*) figuran como Vulnerables (VU). Es oportuno indicar que estas especies dependen de las áreas boscosas para realizar sus actividades vitales, por lo que es vital preservar esas áreas, para la conservación de esta fauna amenazada. En cuanto a aves migratorias sólo se han observado tres (3), la Bijirita (*Setophaga ruticilla*), la Cigüita pega palo (*Mniotilta varia*) y la Cigüita del río (*Parkesia noveboracensis*), todas ellas insectívoras.

Amenazas a la Biodiversidad

Contaminación ambiental, desconocimiento del área protegida y sus normas para el manejo apropiado. Extensión de la frontera agrícola.

Bibliografia:

- Ministerio Ambiente/USAID/TNC/INTEC, 2018. Lista de Especies en Peligro de Extinción, Amenazadas o Protegidas de La Republica Dominicana (Lista Roja Nacional). Ministerio de Medio Ambiente y Recursos Naturales/USAID/TNC/INTEC. Sto. Domingo, República Dominicana. 20 paginas. (Nota: en revisión actualmente)
- Viceministerio de Áreas Protegidas y Biodiversidad. 2018. Plan de Manejo Monumento Natural Pico Diego de Ocampo. Ministerio de Medio Ambiente y Recursos Naturales. Santo Domingo, RD.

MONUMENTO NATURAL SALTO LA TINAJA

Creación: El citado monumento fue incorporado al Sistema Nacional de Áreas Protegidas (SINAP), a través del Artículo 20 del Decreto No. 571-09

Administración: Ministerio de Medio Ambiente y Recursos Naturales

Categoría: Monumento natural

Ubicación: Se crea el Monumento Natural Saltos de la Tinaja con el propósito de recuperar y salvaguardar la caída de agua más hermosa del Río Jacagua, así como el bosque húmedo y los múltiples saltos de menor magnitud que le preceden, en la cuenca alta de este impresionante curso de agua que desciende de las estribaciones meridionales de la Cordillera Septentrional, actualmente sometida a altas presiones por los asentamientos periféricos y su proximidad a la ciudad de Santiago de los Caballeros. Este Monumento Natural abarca un tramo importante del río Jacagua, y los bosques que cubren su cabecera en las estribaciones sur de la Cordillera Septentrional, en el ámbito de la provincia de Santiago de los Caballeros, en el Norte del país.

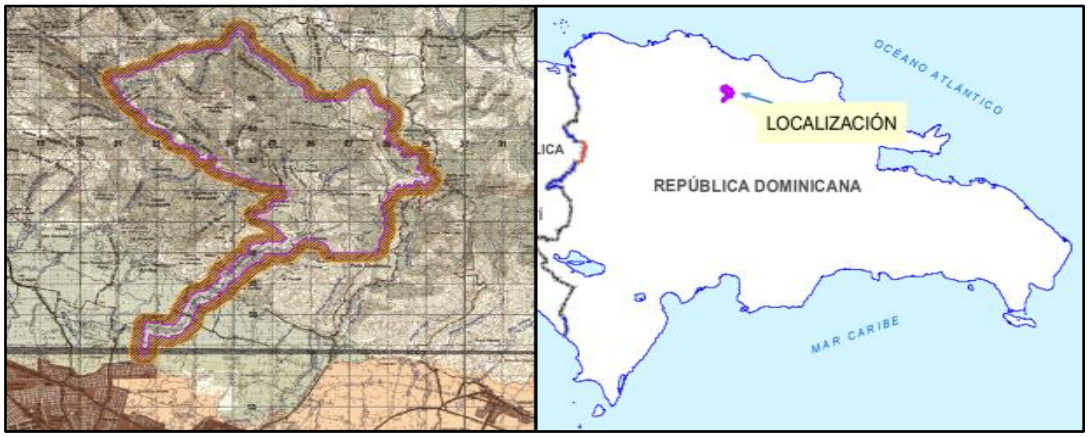

Figura 29. Ubicación del Monumento Natural Saltos de la Tinaja en el terreno.

Topografía, hidrología, clima y paisajes

Este Monumento Natural abarca un tramo importante del río Jacagua, y los bosques que cubren su cabecera en las estribaciones sur de la Cordillera Septentrional, con un perímetro de 29.52 km^2, en el ámbito de la provincia de Santiago de los Caballeros, en el Norte del país. En el tramo del curso del río Jacagua, localizado en el territorio protegido, se conserva una muestra representativa del bosque ribereño, en una buena parte del trayecto del río, este se comporta con forma de cañón o de terrazas encajonadas, donde se posan grandes piedras y lajas compactas de origen marino antiguas. Uno de los aspectos más llamativos, es la gran cantidad de pequeñas cascadas y saltos, con fosas, que vistas desde arriba simulan un recipiente en forma de tinaja, lo que da origen al nombre del Monumento. La zona del curso del río Jacagua, en su fosa en forma de cañón, presenta un microclima con toda la característica de bosque húmedo, con un régimen de lluvia que oscila entre 900 a 1200 milímetros anuales, siendo más seco hacia las estribaciones Sur de la Cordillera Septentrional. La temperatura promedio del orden de los 24ºC. (Ministerio de Medio Ambiente y Recursos Naturales, 2014).

Flora

Se identifican cuatro formaciones naturales principales: Bosque ribereño, Bosque húmedo, Bosque nublado y Pastizales.

Composición florística: En cuanto a la riqueza de la Vegetación en el área de estudio se han registrado 331 especies de plantas vasculares de las cuales 34 son endémicas, 266 nativas, 5 naturalizada y 26 introducidas, pertenecientes a 93 familias de plantas. De las familias identificadas, las que presentan mayor número de individuos son: Moraceae, Myrtaceae Verbenaceae, Arecaceae, Fabaceae, Meliaceae, Poaceae, Asteraceae, Borraginaceae, Mimosaceae. Los géneros más abundante son: *Coccothrinax, Roystoneal, Guarea*, *Ocotea*, Bursera, *Swietenia, Petitia*, *Tetragastris, Trichilia, Eugenias.*

En esta zona se registraron 26 especies amenazadas, que pertenecen a 17 familias.

NOMBRE CIENTIFICO	NOMBRE COMUN	ESTATUS	CATEGORIA DE AMENAZA
Tabebuia obovata	Aceituno	Endemica	EP
Roystonea hispaniolana	Palma real	Endémica	VU
Coccoloba ceibensis	Uva cimarrona	Endémica	
Acrocomia quisqueyana	Corozo	Endémica	PC
Leptogonum buchii	-----	Endemica	PC
Ceiba pentandra	Ceiba	Nativa	VU
Sabal domingensis	Palma cana	Endémica	CR
Swietenia mahagoni	Caoba	Nativa	EP, CITES
Pauteria domingensis	-----	Endemica	VU
Melocactus lemairei	Melón espinoso	Endémica	VU, CITES
Didimopanax tremulus	Pala de viento	Endémica	PC
Amyris elemifera	Guaconejo	Nativa	VU
Maclura tinctorea	Mora	Nativa	EN
Cyrtopodium punctatum	Cañuela	Nativa	EN
Melicoccus jimenezii	Cotoperiz	Endémica	Rara
Ceiba pentandra	Ceiba	Nativa	VU
Caliptranthes biflora	-----	Endemica	PC

Prestoae montana	Manacla	Nativa	VU
Bactris plumeriana	Catey	Endémica	EP
Cedrela odorata	Cedro	Nativa	PC, CITES
Jacaranda poitaei	Abey	Endémica	PC
Scheffle ra tremula	Palo de viento	Endémica	PC
Dendrocereus undatus	Cayuco	Nativa	CR
Vanilla sp.	Vainilla	Nativa	EN, CITES
Tillandsia usneoides	Guajaca	Nativa	VU
Tillandsia setaseae	bromelia	Nativa	VU

Tabla 20. Lista de plantas amenazadas en el Monumento Natural Saltos de la Tinaja

Fauna

Anfibios: Para el Monumento Natural Saltos de La Tinaja, se menciona la presencia de nueve (9) especies de anfibios, 7 de ellas endémicas. Se reportaron los anfibios introducidos, Maco pempem (*Rhinella marina = Bufo marinus*) y la Rana toro (*Lithobates catesbianus= Rana catesbeiana*). En cuanto a anfibios amenazados, se tienen siete (7) : Sapo sureño crestudo (*P. guentheri*), Rana arborícola verde de La Hispaniola (*Hypsiboas heilprini*), la Rana arborícola gigante de La Hispaniola (*Osteopilus vastus*), Calcalí (*E. abbotti*), Rana gigante de La Hispaniola (*E. inoptatus*), Rana de rabadilla roja de La Hispaniola (*E. weinlandi*) y Rana reidora de La Hispaniola (*O. dominicensis*).

Reptiles: De las 16 especies de reptiles reportadas, dos (2) se han naturalizado en la Isla La Hispaniola, una (1) fue introducida y las demás son endémicas. En ese sentido, se puede inferir que el endemismo a nivel de especie es elevado. Las especies, Anolis robusto de La Hispaniola (*Anolis cybotes*), Anolis grácil de La Hispaniola (*Anolis distichus*) y Anolis verde del norte (*Anolis chlorocyanus*), se constituyen en los lagartos más frecuentemente vistos en el areea. Tanto el Anolis de la hierba del desierto (*Anolis olssoni*), Anolis de la hierba de La Hispaniola (*Anolis semilineatus*) como la Ameiva gigante de La Hispaniola (*Ameiva chrysolaema*) figuran en la categoría de amenaza pero de Preocupación Menor (LC), de acuerdo a la Lista Roja de la UICN (2013). Mientras que, en la Lista Roja Nacional del Ministerio Ambiente (2011) figuran las siguientes especies: Lucia del Pico Duarte (*Celestus marcanoi*), Anolis gigante de La Hispaniola (*Anolis baleatus*) y la Boa de La Hispaniola (*Epicrates gracilis*); la primera en categoría de Peligro Critico (PC) y la segunda y tercera En Peligro (EP).

Avifauna: En estudios parciales, se han contado 20 especies de aves, de 8 ordenes y 16 familias. Las especies registradas se dividen en, 19 residentes, cuatro (4) de las cuales son endémicas a las Antillas Mayores, seis (6) endémicas de la Española y una (1) migratoria. Las especies endémicas mas comunes son Cigua palmera (Dulus dominicus), el Carpintero (Melaner pesstriatus) y el Cuatro ojos (Phaenicophilus palmarum). Todas estas endémicas tienen un estatus de común o abundante, con poblaciones estables y amplia distribución en toda la República Dominicana. Entre todas las especies registradas, solo una presenta estatus, no oficial, de Amenazada para la Hispaniola, la Perdiz colorada (Geotrygon montana). Esta especie se caza excesivamente.

Amenazas a la Biodiversidad

La caza furtiva disminución de hábitats (pérdida y fragmentación), para el desarrollo de actividades antropicas como: agricultura migratoria, ganadería, expansión demográfica, debido a la falta de un ordenamiento territorial. De igual manera, el cambio climático, presencia de especies introducidas de fauna, comercio ilegal de especies, básicamente con fines de mascota y comercial, así como las creencias mágico-religiosas y culturales, sobre todo, el grupo de las culebras.

Bibliografía consultada

- Ministerio de Medio Ambiente y Recursos Naturales, 2014. Evaluación de la Biodiversidad en el Monumento Natural Salto la Tinaja, Provincia Santiago de los Caballeros. Santo Domingo, República Dominicana.63p

MONUMENTO NATURAL. SALTO DE JIMENOA

Creación: Decreto 571-09[43]
Administración: Ministerio de Medio Ambiente y Recursos Naturales
Categoría: Monumento natural
Ubicación: Jarabacoa, Provincia de la Vega.[44]

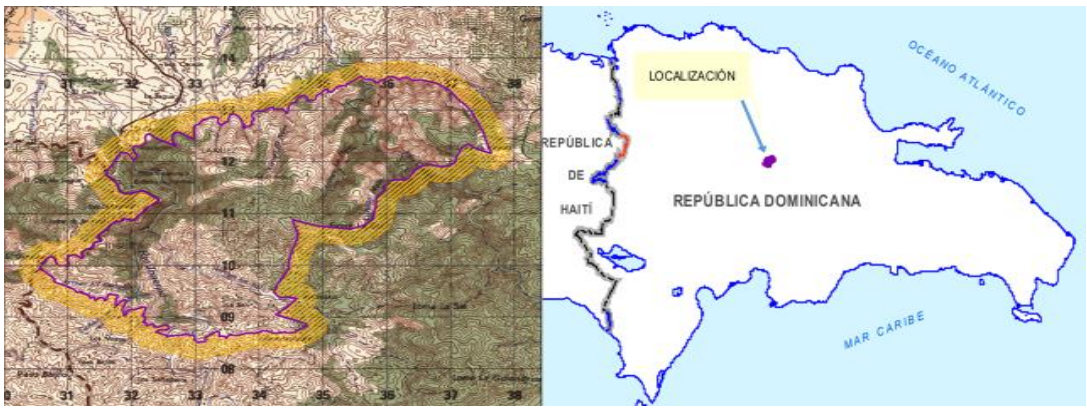

Figura 30. Ubicación del Monumento Natural Salto de Jimenoa

Características generales:

Esta área protegida será debidamente habilitada, dentro de las normas establecidas para la Categoría III de la Unión Mundial para la Naturaleza, para aprovechar la gama infinitas de servicios ambientales, recreativos y educativos que se conjugan o asocian a la benignidad del clima tan singular de esta zona geográfica del país y

[43] http://ambiente.gob.do/wp-content/uploads/2016/10/Monumento-Nacional-Salto-de-Jimenoa.pdf
[44] Idem

la diversidad florística que atesora. [45] El Monumento Natural Salto de Jimenoa, se encuentra cinco kilómetros antes de llegar a la entrada a Jarabacoa; no existe un acceso regular al mismo, por lo cual los viajeros deben recurrir a un vehículo de motor (taxi, moto concho, otros). Posee una extensión de 17.43 km^2. El conjunto se compone de dos saltos: Salto de Jimenoa Uno, y Salto de Jimenoa Dos. Las formaciones rocosas que yacen en su lecho o se levantan en sus orillas, la playa que se extiende bajo la cascada, los charcos que dejan la corriente y la diversidad de plantas y animales nutren su ecosistema. Rodríguez (2013).

Nota: No disponible otras informaciones a partir de la bibliografía y fuentes consultadas

Bibliografía consultada:

- Kenia Rodríguez (2013). Plan de manejo del ecoturismo Monumento Natural "Salto de Jimenoa II". Pontificia Universidad Católica Madre y Maestra. Facultad de Ciencias Sociales y Administrativas. Departamento de Administración Hotelera.

REFUGIO DE VIDA SILVESTRE CAÑÓN DEL RÍO GURABO

Creación: el Decreto 571-09

Administración: Ministerio de medio ambiente y Recursos naturales

Categoría: Refugio de Vida Silvestre

Ubicación: El área protegida correspondiente al Cañón de Gurabo, ocupa una superficie de 30.16 km^2. Está limitada al norte por la carretera Mao-Santiago Rodríguez, al este, corre paralelo a la carretera que va a Monción, desde El Cruce de Los Quemados; éste límite está sobre el arroyo denominado Arroyo Hondo, afluente del Río Gurabo y atraviesa las comunidades de Los Quemados, El Higuito y Arroyo de Agua. Al sur, corre sobre una cañada denominada Cañada Grande, próximo a las localidades del Monte Chispero, Monte Higuito y Monte de la Gallina, a oeste, carretera Mao-Santiago Rodríguez y camino que va de esta carretera a las comunidades de La Estancia y Gurabito, atravesando por las comunidades de Los Caimoníes y El Orégano". (Viceministerio de Áreas Protegidas y Biodiversidad, 2018). El área protegida "Refugio de Vida Silvestre Cañón del Río Gurabo" se localiza a lo largo del Río (y Furnia) de Gurabo, el cual delimita las provincias Valverde y Santiago Rodríguez, República Dominicana. Se accede desde la carretera que comunica Monción desde el cruce de Los Quemados, y queda a aproximadamente hora y media desde Santiago de los Caballeros. N19.491712° W71.177280°.[46]

[45] https://www.accionverde.com/monumento-nacional-salto-de-jimenoa/
[46] https://www.rufford.org/files/Listado%20de%20la%20Avifauna.pdf

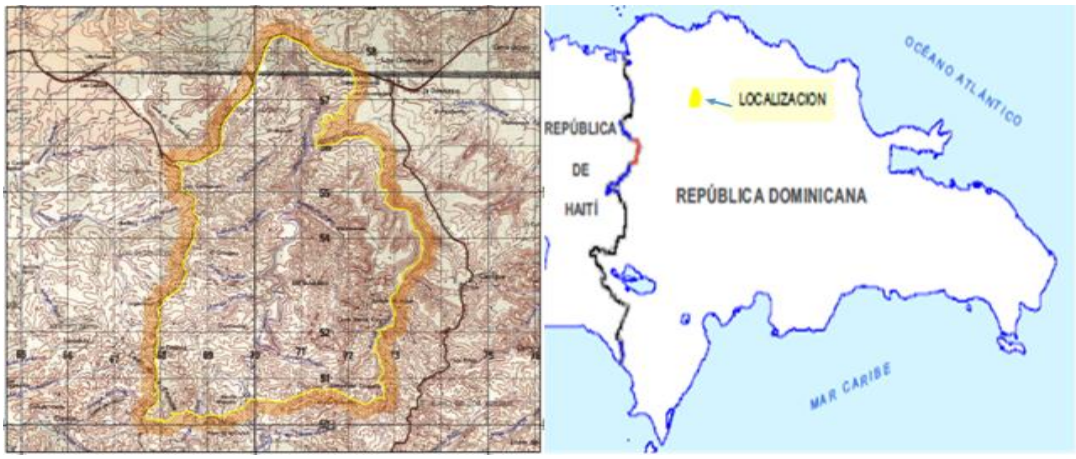

Figura 31. Ubicación del Refugio de Vida Silvestre Cañón del Río Gurabo [47]

Topografía, hidrología, clima y paisajes

Dentro de esta área protegida tenemos que la principal fuente hídrica corresponde al rio Gurabo, que drena sus aguas directamente al río Yaque del Norte. Dentro del área su cauce principal en su punto más alto alcanza los 383 msnm, descendiendo hasta los 200 msnm en la parte más baja, siguiendo su curso fuera del área hasta hacer confluencia con el rio Yaque del Norte en elevación de 50 msnm. Dentro de los afluentes principales que drenan sus aguas al rio Gurabo en la zona de estudio están los arroyos: de Agua, Hondo, Palero, Cabra y Gurabito. Es notable la presencia de los vientos alisios modificados por la Cordillera Septentrional y en promedio temperatura anual de 26ºc.

El Cañón del Río Gurabo, más conocido como la Furnia de Gurabo; con formaciones del Periodo Geológico del Mioceno, está constituido por plegamientos y estratificaciones de sedimentos de depósitos de aguas poco profundas, que se mezclaron con una rica fauna marina, generando sedimentos.

Composición del área incluye Bosque Seco, localizado en la parte sureste del Refugio, con una elevación de 378 msnm, suelos superficiales con afloramiento rocoso, arcilloso, calcárea y depósito marino de formación Gurabo. Ocupa una superficie de 13.27 km² del total del área protegida, para un 44.0% de su territorio. El estrato arbóreo está compuesto por especies cuya altura oscila entre 5 y 8 metros, las más comunes son Guayacán (*Guaiacum officinale*), Carga agua (*Erythroxylum rotundifolium*), Candelón (*Acacia skleroxyla*), Cayuco (*Pilosocereus polygonus*), Campeche (*Haematoxilom campechianum*), Canelilla (*Myrciantes fragrans*) y Canela de la tierra (*Canella winterana*), esta última melífera y muy abundante. En este lugar se observan algunos individuos del Guaney (*Zombia antillarum*) el cual es endémico y crece en suelos serpentinos.

Flora:

En cuanto a la riqueza de la vegetación en el área fueron observadas 279 especies de plantas vasculares de las cuales 29 son endémicas, 237 nativas de la isla Española, dos (2) naturalizadas y 11 introducidas, distribuidas todas en 78 familias de plantas. Es importante señalar que en el área existe un 10% de endemismo del total de las especies observada en los diferentes ambientes. Las familias más abundante son: Moraceae, Myrtaceae Verbenaceae, Fabaceae, Euphorbiaceae, Malvaceae, Poaceae, Asteráceae, Borragináceae, Mimosaceae. Los géneros más abundante son: Coccothrinax, Sabal, Bursera, Canella, Tetragastris, Guaiacum, Trichilia, Eugenias (Viceministerio de Áreas Protegidas y Biodiversidad, 2018). En el área se reportan 32 especies amenazadas, pertenecientes a 12 familias. Por su estatus biogeográfico, se distribuyen de la siguiente manera: 11 endémicas y 20 nativas. Ocho (8) de estas especies están en la Lista Cites (Viceministerio de Áreas Protegidas y Biodiversidad, 2018).

[47] http://ambiente.gob.do/wp-content/uploads/2016/10/RVS-Canon-del-Rio-Gurabo.pdf

NOMBRE CIENTIFICO	NOMBRE COMUN	ESTATUS	CATEGORIA DE AMENAZA
Roystonea hispaniolana	Palma real	Endémica	VU
Zombia antillarum	Guanillo	Endémica	PC
Krugiodendron ferreum	Quiebra hacha	Nativa	PC
Sabal domingensis	Palma cana	Endémica	CR
Swietenia mahagoni	Caoba	Nativa	EP, CITES
Canella winterana	Canela de tierra	Nativa	VU
Consolea monilifornis	Alpargata	Nativa	VU
Melocactus lemairei	Melón espinoso	Endémica	VU, CITES
Leptocereus weingartianus	Cayuco	Endémica	EN
Pilosocereus polygonus	*Cayuco*	Endémica	VU
Amyris elemifera	Guaconejo	Nativa	EN
Maclura tinctorea	Mora	Nativa	EN
Cyrtopodium punctatum	Cañuela	Nativa	EN
Opuntia antillarum	Tuna	Nativa	VU
Coccoloba leoganensis	Uva cimarrona	Endémica	Rara
Pseudophoenix vinifera	Cacheo	Endémica	PC
Opuntia dillenii	Tuna brava	Nativa	VU ,CITES
Coccothrinax fragrans	Guanito	Nativa	EN
Cedrela odorata	Cedro	Nativa	PC, CITES
Anonna reticulata	Mamón	Nativa	EN
Zanthoxylum bifoliolatum	pino	Nativa	EN
Petitia domingensis	Capa de sabana	Nativa	VU
Oeseoclades maculata	Orquídea africana	Naturalizada	CITES
Agave antillarum	Maguey de bestia	Endémica	EN
Mammillaria prolifera	Bombillito	Nativa	VU, CITES
Guaiacum officinale	Guayacán	Nativa	PC, CITES
Guaiacum sanctum	Guayacancillo	Nativa	VU, CITES
Vanilla sp.	Vainilla	Nativa	
Dendrocereus undatus	Cayuco	Nativa	CR, CITES
Tillandsia usneoides	Guajaca	Nativa	VU
Ateleia microcarpa	Azota potranca	Endémica	CR
Harrisia divaricata.	Yasa	Endémica	EN,CITES

Tabla 21. Especies amenazadas de plantas en la Furnia de Gurabo. (Viceministerio de Áreas Protegidas y Biodiversidad, 2018)

Nota

FV (Forma de Vida): A-árbol o arborescente; Ar-arbusto o arbustivo; H-Hierba terrestre; HE-Hierba epifita; L-Liana.

Categorías de Amenaza (CE): EP: En Peligro, PC: Peligro Crítico, VU: Vulnerable.

Fuente: Lista Roja de Plantas Silvestres Amenazadas de la República Dominicana, 2011.

Fauna

En el área se reportan 11 especies de anfibios, de ellas, cinco (5) especies endémicas, pertenecientes al orden Anura y a las familias Bufonidae, Eleutherodactylidae, Hylidae y Ranidae. (Gabot-Rodríguez, E., & Marte, C. ,2019); (Viceministerio de Áreas Protegidas y Biodiversidad, 2018).

Anfibios y reptiles amenazados Refugio de Vida Silvestre Furnia de Gurabo		
Grupo/Especie	Fuentes	
Anfibios	UICN	MA
Hypsiboas heilprini	VU	VU
Osteopilus pulchrilineatus	EN	EP
Osteopilus vastus	EN	EP
Reptiles		
Trachemys stejnegeri		VU
Totales de especies 4	3	4

Tabla 22. Anfibios y reptiles amenazados[48]. (Viceministerio de Áreas Protegidas y Biodiversidad, 2018).

[48] https://novitatescaribaea.do/index.php/novitates/article/view/195/172

Dentro de las aves se señala la presencia de 67 especies, de ellas 13 endémicas de la Isla La Española , la Cigua palmera (Dulus dominicus), nuestra Ave Nacional, el Cuatro ojos (*Phaenicophilus palmarum*), Pájaro bobo (*Coccyzus longirostris*), Barrancolí (*Todus subullatus*), Carpintero (*Melaner pesstriatus*), el Carpinterito de sierra (*Nesoctites icromegas*), así como también el Torico (*Siphonorhis brewsteri*), Pitangua (*Antrostomus ekmani*), Cigüita juliana (*Víreo nanus*), Maroita (*Contopus hispaniolensis*), Lechuza cara ceniza (*Tyto laucops*), Cotorra (*Amazona ventralis*) y la Cigua canaria (*Icterus dominicensis*). (Viceministerio de Áreas Protegidas y Biodiversidad, 2018).

Con relación a aves amenazadas, se registraron un total de nueve (9) especies**,** que son: la Lechuza de sabana (*Asio flammeus*) en Peligro Critico (PC), dos (2) en Peligro (EP), el Búcaro (*Burhinus bistriatus*) y el Torico (Siphonorhis brewsteri), mientras el Guaragüaito de sierra (*Accipiter striatus*), la Perdis (*Geotrygon chrysia*), Paloma ceniza (*Patagioenas inornata*), Paloma coronita (*P. leucocephala*), Cotorra (*Amazona ventralis*) y la Cigua canaria (*Icterus dominicensis*) están en la categoría de Vulnerable (VU). En cuanto a aves migratorias, se han registrado 13 especies, entre las cuales están: la Bijirita (*Setophaga ruticilla*), Cigüita tigrina (*S. tigrina*), Cigüita de los prados (*Setophaga discolor*), Cigüita del café (*S. caerulescens*), Pega palo (*Mniotilta varia*), Cigüita parula (*Parula americana*), Cigüita saltarina (*Parkesia aurocapillus*) y Cigüita del rio (*P. noveborascensis*), entre otras.

Amenazas a la Biodiversidad

Durante años, la Furnia del río Gurabo fue escenario de caza indiscriminada de la Paloma morada dado el habito de esta de viajar desde lugares muy distantes, en un fenómeno posiblemente único en la República Dominicana, para consumir material fósil de las paredes de la furnia, en un fenómeno no muy bien aclarado, donde al parecer las aves obtienen ciertos suplementos de calcio. Entre los peligros actuales están precisamente, la caza furtiva, además de la presión de las comunidades circundantes, la ganadería y la desforestación de todo el entorno de la reserva.

Bibliografía consultada

- Gabot-Rodríguez, E., & Marte, C. (2019). Inventario rápido de los reptiles del refugio de vida silvestre El Cañón del río Gurabo, República Dominicana. *Novitates Caribaea*, (13), 117-121. https://doi.org/10.33800/nc.v0i13.195.
- MINISTERIO DE MEDIO AMBIENTE Y RECURSOS NATURALES, Viceministerio de Áreas Protegidas y Biodiversidad, Departamento de Vida Silvestre, octubre 2016. Evaluación Ecológica Rapada de la Biodiversidad y Cartografía en el Refugio de Vida Silvestre Furnia de Gurabo, Provincia Santiago Rodríguez, Santo Domingo, República Dominicana.
- Viceministerio de Áreas Protegidas y Biodiversidad (2018). Plan de Manejo Refugio de Vida Silvestre Cañón del Rio Gurabo .MINISTERIO DE MEDIO AMBIENTE Y RECURSOS NATURALES. VICEMINISTERIO DE ÁREAS PROTEGIDAS Y BIODIVERSIDAD. DIRECCIÓN DE ÁREAS PROTEGIDAS. Abril 2018.

REFUGIO DE VIDA SILVESTRE RIO CHACUEY

Creación: Mediante la Ley 202-04
Administración: Ministerio de Medio Ambiente y Recursos Naturales
Categoría: Refugio de vida silvestre
Ubicación: Refugio de Vida Silvestre "Río Chacuey" Creado mediante Ley 202-04, tiene 38.77 km^2. El municipio de Dajabón tiene 12 km^2 (4.14 %) de su territorio ocupado por esta área protegida, el área restante se halla en la provincia de Montecristi. El refugio esta conformado por el embalse artificial de la presa de Chacuey, rodeado de áreas de bosque seco, que atrae numerosas aves. En el lago de la presa se desarrolla cierta actividad pesquera. Esta categoría de área protegida corresponde a la Categoría IV de la UICN, definida como: "Área terrestre y/o marina sujeta a intervención activa con fines de manejo, para garantizar el mantenimiento

de los hábitat y/o satisfacer las necesidades de determinadas especies.“[49] (Caracterización ambiental de la provincia de Dajabón, 2010).

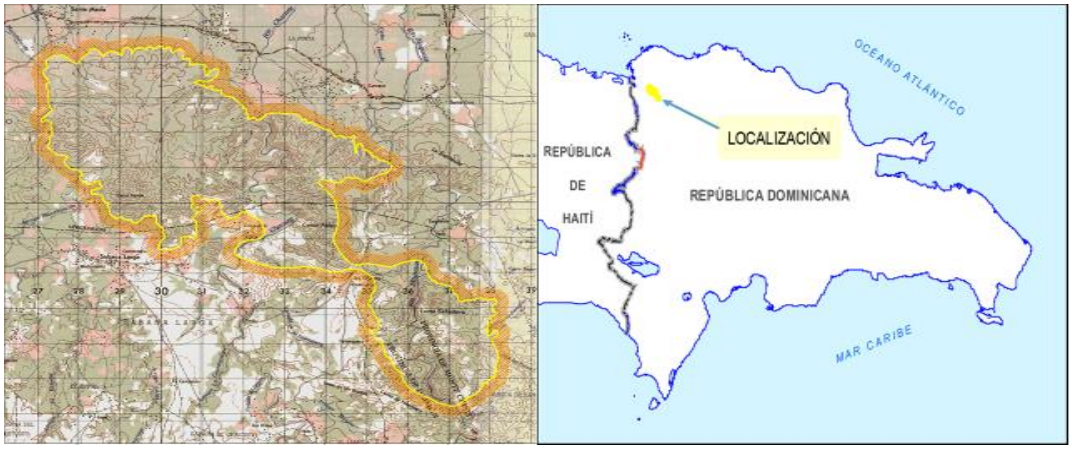

Figura 32. Refugio de Vida Silvestre “Río Chacuey”[50]

Características generales: Según el mapa de uso y cobertura 2003, los usos en la porción correspondiente a la provincia de Dajabón son la agricultura mixta, el pasto para ganado, el bosque y matorral seco. Si bien la mayor parte de la superficie de este refugio corresponde al territorio de Montecristi, Dajabón tiene enorme incidencia en su existencia y permanencia, puesto que desde esta provincia se produce el agua que nutre el refugio y asegura el ecosistema (Caracterización ambiental de la provincia de Dajabón, 2010).

Figura 33. Área de la presa del Rio Chacuey. Área del Refugio de Vida silvestre. (Caracterización ambiental de la provincia de Dajabón, 2010).

[49] https://ecohis.jmarcano.com/areas-protegidas/sistema-areas-protegidas/areas-manejo/
[50] http://ambiente.gob.do/wp-content/uploads/2016/10/RVS-Rio-Chacuey.pdf

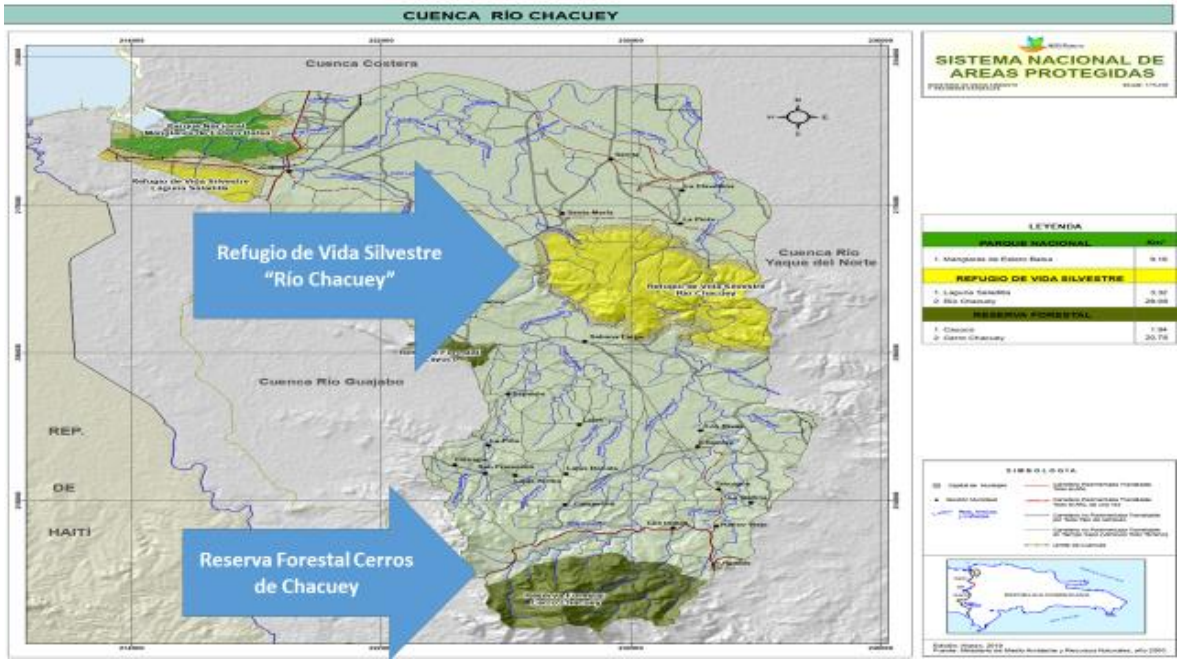

Figura 34. Ubicación de las áreas protegidas Reserva Forestal Cerros de Chacuey y Refugio de vida silvestre Rio Chacuey, ubicadas ambas en la Cuenca del Rio Chacuey.

Comentarios: no disponibles otras informaciones a partir de la bibliografía y las fuentes consultadas

Bibliografía

- Caracterización ambiental de la provincia de Dajabón, 2010. Ministerio de Medio Ambiente y Recursos Naturales - GIZ. Programa "Gestión y protección de recursos naturales en cuencas hidrográficas" PROGEREN III. 2010. 120p. https://www.academia.edu/683778/Caracterizaci%C3%B3n_Ambiental_de_la_Provincia_Dajab%C3%B3n_R.D

.

RESERVA NATURAL ALTO BAO

Creación: LEY 202-04

Administración: Ministerio de Medio Ambiente y Recursos Naturales

Categoría: Reserva Natural

Ubicación: El Valle de Bao, uno de los valles intramontañosos más altos e importantes de la Cordillera Central, R.D., se ubica en el camino hacia el Pico Duarte. Reserva Forestal,

Características generales: Este valle intramontano, en forma de hoya, tiene unos dos kilómetros de largo, es uno de los intramontañosos de mayor altura de la isla, rodeado de un tupido bosque de Pino criollo con una base de Pajón, el cual puede amanecer congelado en la época más fresca y es aquí donde nace uno de los ríos más importantes del país, el Bao. Ubicado a 1,800 metros sobre el nivel del mar, ofrece al visitante un respiro y refugio para los montañistas que van camino al Pico Duarte. Se observa una amplia distribución de la graminea denominada Pajón (*Danthonia domingensis*) y la especie *Deschampsia domingensis*, endémicas de La Española. Una evaluación del 2007 recomienda realizar estudios más específicos sobre la flora, la ejecución de actividades compatibles con la protección como proyectos agroforestales, con plantas nativas en la periferia del parque y sus comunidades, regular la cantidad de visitantes, principalmente con caballos y mulos, entre otras cosas.[51] Entre las áreas con más pérdidas forestal entre el año 2000 y el 2014, con poco más de 17 km^2 de bosques perdidos.[52] Superficie de 614.6 km^2, (307.3 en San José de las Matas y 307.3 en Janico)[53]

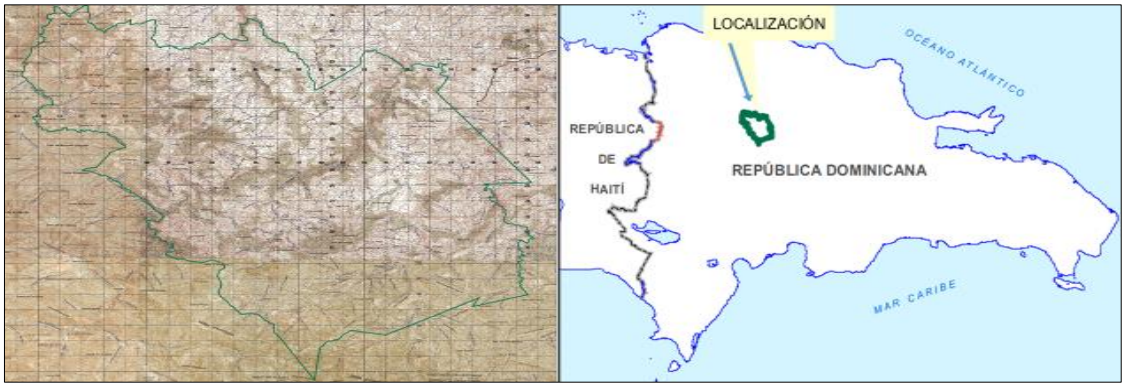

Figura 35. Contorno y ubicación de la Reserva Natural Alto Bao.[54]

Figura 36. Vista del Alto Bao, con predominio de la graminea "Pajon" y al fondo Pino criollo *(Pinus occidentalis)*[55]

Nota: No disponible otras informaciones a partir de la bibliografía y fuentes consultadas

---

[51] https://www.diariolibre.com/actualidad/medioambiente/el-valle-del-bao-destino-importante-para-la-conservacion-y-el-ecoturismo-HJ9038898

[52] https://www.geografiafisica.org/2016/03/26/las-9-areas-protegidas-que-mayor-cantidad-absoluta-de-cobertura-boscosa-han-perdido-entre-2000-y-2014/

[53] https://www.academia.edu/37257556/%C3%81reas_protegidas_seg%C3%BAn_las_leyes_174_09_y_202_04_y_el_Decreto_571_09_por_Regiones

[54] http://ambiente.gob.do/wp-content/uploads/2017/12/Reserva-Forestal-Alto-Bao.pdf

[55] https://porelojodelacerradura.com.do/el-valle-del-bao-destino-importante-para-la-conservacion-y-el-ecoturismo/

RESERVA NATURAL. ALTO MAO

Creación: LEY 202-04

Administración: Ministerio de Medio Ambiente y Recursos Naturales

Categoría: Reserva Natural

Ubicación: San José de las Matas. Reserva Forestal, superficie de 457.1km^2 [56]

Características generales: Entre las áreas protegidas que mayor cantidad absoluta de cobertura boscosa han perdido entre 2000 y 2014 con 40 km^2 de superficie boscosa perdida, casi 65,000 tareas.[57]

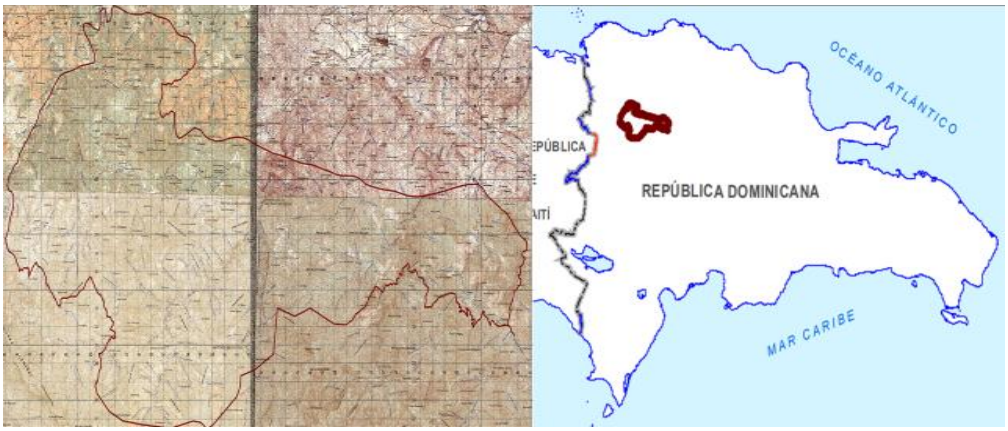

Figura 37. Ubicación de la Reserva Natural Alto Mao**.** [58]

Nota: No disponible otras informaciones a partir de la bibliografía y fuentes consultadas

[56] https://www.academia.edu/37257556/%C3%81reas_protegidas_seg%C3%BAn_las_leyes_174_09_y_202_04_y_el_Decreto_571_09_por_Regiones

[57] https://www.geografiafisica.org/2016/03/26/las-9-areas-protegidas-que-mayor-cantidad-absoluta-de-cobertura-boscosa-han-perdido-entre-2000-y-2014/

[58] http://ambiente.gob.do/wp-content/uploads/2017/12/Reserva-Forestal-Alto-Mao.pdf

RESERVA NATURAL RIO CANA

Creación: LEY 202-04

Administración: Ministerio de Medio Ambiente y Recursos Naturales

Categoría: Reserva Natural

Ubicación:

Características generales: Entre las áreas protegidas que mayor cantidad absoluta de cobertura boscosa han perdido entre 2000 y 2014 con 17 km^2 de superficie boscosa perdida. En este caso, llama la atención el patrón geométrico: talas sobre grandes superficies continúas con límites rectilíneos, sugiriendo acciones planificadas.

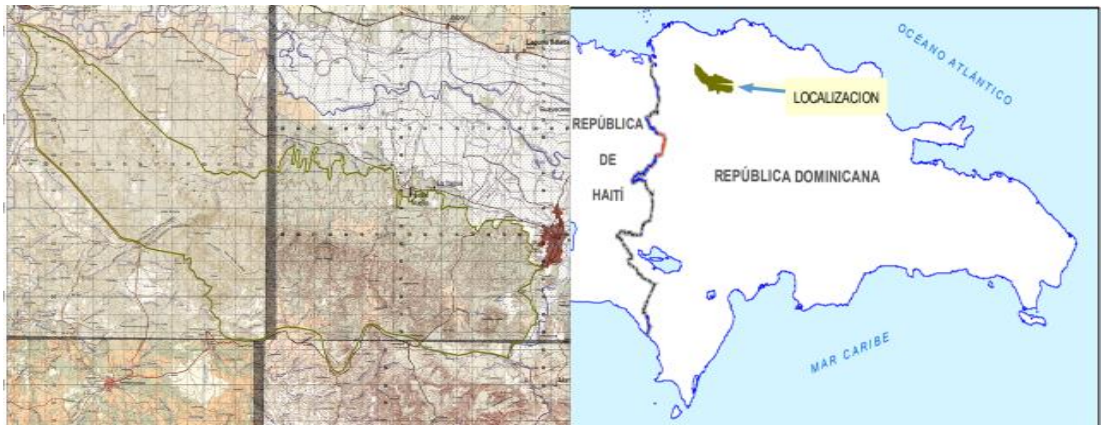

Figura 38. Reserva natural Rio Cana.[59]

Nota: No disponible otras informaciones a partir de la bibliografía y fuentes consultadas

[59] Idem

RESERVA NATURAL CERROS DE CHACUEY

Creación: Mediante la Ley 121-03

Administración: Ministerio de Medio Ambiente y Recursos Naturales

Categoría: Reserva Natural

Ubicación: La Reserva Forestal Cerros de Chacuey se encuentra en la provincia de Dajabón, fronteriza con Haití, en el noroeste de la República Dominicana. Tres (3) municipios de esta provincia comparten el territorio de la Reserva Forestal que son: Partido, Loma de Cabrera y El Pino. Del territorio total de la reserva 33.64 km^2 pertenecen al municipio de Partido (el 64% de la Reserva), 16.68 km^2 a Loma de Cabrera (31%) y 1.57 km^2 (3%) a El Pino. (Viceministerio de Áreas Protegidas y Biodiversidad. 2013).

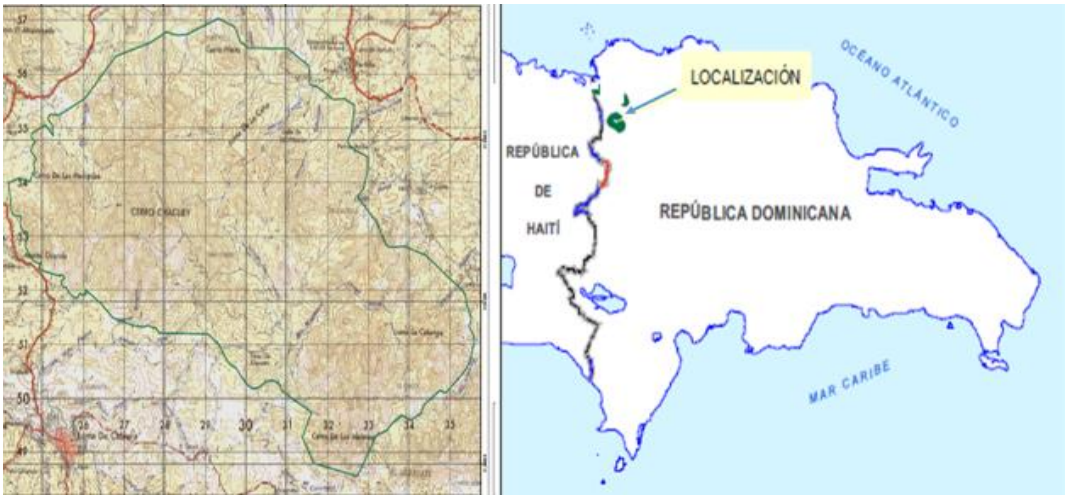

Figura 39. Ubicación de la Reserva Forestal Cerros de Chacuey en la provincia de Dajabón[60]

Topografía, hidrología, clima y paisajes

Según datos del clima de las estaciones de la Oficina Nacional de Meteorología, mas cercanas a esta reserva (Dajabón y Restauración) la precipitación anual oscila alrededor de los 1363mm, mientras la temperatura promedio es de entre 26 y 27.1^{0}C. Las zonas de vida en el área de la reserva son el Bosque húmedo subtropical y Bosque muy húmedo subtropical. Paradójicamente en laregion fuera de la reserva, se encuentra áreas de Bosque seco. Son notables en el paisaje los Bosques de Pino (*Pinus occidentalis*), Bosque latifoliados húmedos y ribereños, Matorrales sobre roca de serpentina y ecosistemas antropizados (poteros, pastizales y cultivos menores).[61] (Viceministerio de Áreas Protegidas y Biodiversidad. 2013).

El área toda esta constituida de una serie de cerros que son parte de las estribaciones más noroccidentales de la Cordillera Central, predominando el Cerro Chacuey con 810 msnm, Las Mercedes 463 msnm y Las Cañas 320 msnm. Los ríos y cañadas que nacen en la Reserva Forestal Cerros del Chacuey alimentan las cuencas de los ríos Chacuey y Maguaca que nacen en sus áreas, así como la de los ríos Guayubin y Masacre, este último , que define la frontera con Haití. Tanto el Chacuey, Maguaca y Guayubin drenan a su vez hacia el rio Yaque del norte, antes de desembocar en la Bahía de Manzanillo. (Viceministerio de Áreas Protegidas y Biodiversidad. 2013). Es importante precisar que en la Reserva Forestal Cerro Chacuey, nacen siete de los trece ríos o arroyos que suministran agua potable a Dajabón: Maguaca, Chacuey, Arroyo Azul, Tireo, Arroyo Bonito, El Corozo y Cemitren (Caracterización ambiental de la provincia de Dajabón, 2010).

Flora

En la reserva Cerros de Chacuey, se reportan 468 especies de plantas vasculares, correspondientes a 297 géneros y 93 familias. Las familias con mayor cantidad de especies son Rubiaceae con 29, Myrtaceae con 24, Euphorbiaceae con 22, Asteraceae con 20, Fabaceae con 18 y Melastomataceae con 14. El estatus biogeográfico incluye 75 especies endémicas, 368 nativas, 17 naturalizadas, 13 introducidas y 5 especies han sido identificadas solo hasta el nivel de género. De todas estas especies, 22 se reportan como amenazadas en la Lista Roja de la Republica Dominicana, en los aprendices de la Convención sobre el Comercio Internacional

[60] http://ambiente.gob.do/wp-content/uploads/2017/12/Reserva-Forestal-Cerros-de-Chacuey.pdf
[61] http://descifrandolanoticia.com/el-cerro-de-chacuey-gran-pulmon-ecologico-de-la-region-norte

de Especies Amenazadas de Fauna y Flora Silvestres (CITES) o la Lista Roja de la Unión Internacional para la Conservación de la Naturaleza (UICN), de ahí, nueve especies de orquídeas. (Viceministerio de Áreas Protegidas y Biodiversidad. 2013)

Figura 40. Vista del Reserva Forestal Cerros de Chacuey Dajabón.

Fauna

En la reserva se reportan siete especies de anfibios de los órdenes Anura y las familias Bufonidae, Eleutherodactylidae, Hylidae y Ranidae. De estas especies , dos son introducidas: el Maco pempem (*Rhinella marina = Bufo marinus*) y la Rana toro (*Lithobates catebianus = Rana catesbiana*). Ambas se mencionan con capacidad como especies invasoras.

Con respecto a los reptiles, se han reportado en la reserva 114 especies, representantes del orden Squamata y las familias: Amphisbaenidae, Anguidae, Boidae, Dactyloidae, Dipsadidae, Leiocephalidae, Sphaerodactylidae y Typhlopidae. Los lagartos arborícolas fueron los más frecuentes, entre ellos: Anolis robusta de la Hispaniola (*Anolis cybotes*) y Anolis verde del norte *(Anolis chlrocyanus*). Como reptiles amenazados se mencionan a Anolis gigante dominicano (Anolis baleatus) y la Boa de la Hispaniola (*Epicrates striatus*).

La avifauna está representada en la reserva por 28 especies de 16 familias y 25 géneros, de los cuales 13 son residentes, tres migratorias, dos introducidas y 10 endémicas. De estas últimas, se reportan: la Cigua palmera (*Dulus dominicus*), el Ave Nacional; el Pajaro Bobo *(Coccysus longirostris =Saurothera longirostris);* Barrancoli (*Todus subulatus*); Chicuí *(Todus angustirrostris),* el Carpintero *(Melanerpes striatus);* Cuatro ojos *(Phaenicuphilus palmarum);* Perico *(Araqtinga chloroptera);* Cuervo *(Corvus leucognaphalus);* Cao *(Corvus palmarum)* y el Carpintero de Sierra *(Nesoctites micromegas)*.

Amenazas a la Biodiversidad:

En el Cerro Chacuey y su entorno tradicionalmente se han desarrollado actividades económicas incompatibles con los objetivos de conservación del área protegida, siendo la ganadería la más problemática, creando impactos negativos como la destrucción del bosque para la siembra de yerba y la contaminación de las aguas por el ganado. El corte de madera se realiza tanto para la expansión de las parcelas ganaderas, como para la agricultura, así también se realiza la extracción de cuaba del pino, actividad que afecta de manera considerable la vegetación de esta especie.

Bibliografía:

- Caracterización ambiental de la provincia de Dajabón, 2010. Ministerio de Medio Ambiente y Recursos Naturales - GIZ. Programa “Gestión y protección de recursos naturales en cuencas hidrográficas” PROGEREN III. 2010. 120p. https://www.academia.edu /683778/ Caracterizaci %C3%B3n _ Ambiental_de_la_Provincia_Dajab%C3%B3n_R.D
- Viceministerio de Áreas Protegidas y Biodiversidad. 2013. Plan de Manejo Reserva Forestal Cerros de Chacuey. Ministerio de Medio Ambiente y Recursos Naturales, Santo Domino RD. 64p.

RESERVA NATURAL LAS MATAS

Creación: LEY 202-04

Administración: Ministerio de Medio Ambiente y Recursos Naturales

Categoría: Reserva Natural

Ubicación: Montecristi.

Características generales: Reserva forestal

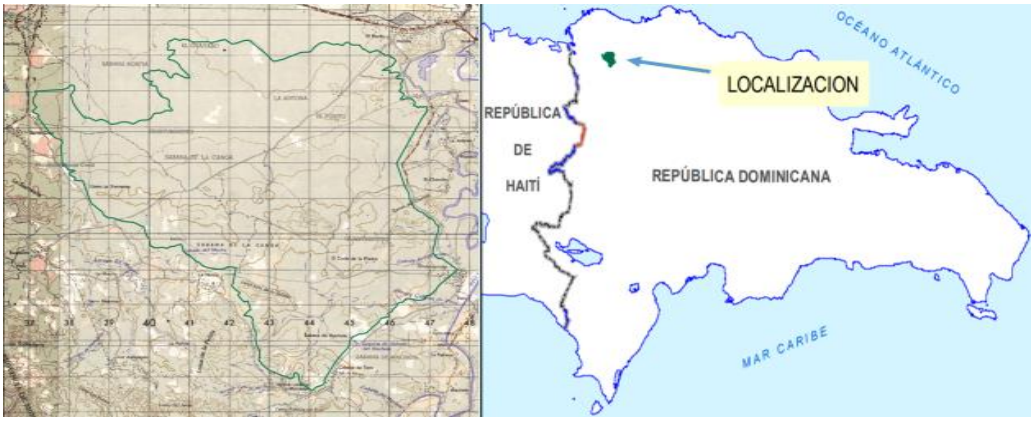

Figura 41. Ubicación de la Reserva Natural Las Matas.[62]

Nota: No disponible otras informaciones a partir de la bibliografía y fuentes consultadas

PAISAJES PROTEGIDOS[63]

- ***Carretera El Abanico-Constanza***: con los límites y superficie que se describen a continuación: a su paso por la loma de Cazabito de la Cordillera Central, con una franja de 100 metros de ancho en los valles y llanuras, y de 250 metros en las zonas montañosas, medidos en ambos casos a partir de los taludes de cada lado de la vía. El polígono antes descrito encierra una superficie de aproximadamente 15 Km².

- ***Carretera Santiago-La Cumbre-Puerto Plata***: con los límites y superficie que se describen a continuación: se establece el punto de partida en las coordenadas UTM 325400 ME y 2154700 MN localizada al salir de Gurabo de donde se continúa en dirección noroeste por la carretera hacia Puerto Plata pasando por La Cumbre y Yásica Abajo manteniendo una separación de 250 metros a ambos lados de la misma hasta tocar las coordenadas UTM 330255 ME y 2181100 en el Cruce de la Gran Parada con la carretera Sosúa-Puerto Plata. El polígono antes descrito encierra una superficie de aproximadamente 11.5 Km²

- ***Carretera Bayacanes-Jarabacoa***: con los límites y superficie que se describen a continuación: se establece el punto de partida en las coordenadas UTM 233900 ME y 2127700 MN, continuando luego por la carretera que comunica Bayacanes con Jarabacoa manteniendo una separación de 500 metros a ambos lados de la misma hasta llegar a las coordenadas UTM 327850 ME y 211600 MN. El polígono antes descrito encierra una superficie de aproximadamente 4.8 Km².

- ***Entrada de Mao***: con los límites y superficie que se describen a continuación: se establece el punto de partida en las coordenadas UTM 281500 ME y 2155850 MN, de donde se sigue la delimitación en dirección este por el pie de monte del bosque localizado al norte de las comunidades de Martínez con Entrada de Mao hasta tocar las coordenadas UTM 288000 ME y 2154550 MN, de donde se sigue la delimitación en dirección noroeste al pie del bosque de la parte alta de arroyo Los Posos y siguiendo por el pie de la loma Sierrecita de donde se sigue bordeando todo el bosque existente al oeste del río Amina hasta llegar al sur de la carretera que comunica a Amina con Hato Nuevo de donde se sigue todo al pie del bosque localizado al sur de la referida carretera hasta tocar las coordenadas UTM 284000 ME y 2163500 MN, de donde se

[62] http://ambiente.gob.do/wp-content/uploads/2017/12/Reserva-Forestal-Las-Matas.pdf

[63] https://www.academia.edu/37257556/%C3%81reas_protegidas_seg%C3%BAn_las_leyes_174_09_y_202_04_y_el_Decreto_571_09_por_Regiones

sigue la delimitación en dirección suroeste por el pie del bosque localizado al este del río Mao y en Jiménez cambia al este hasta tocar el punto de partida en las coordenadas UTM 281500 ME y 2155850 MN.